Identificativo: GARI BIO Rev.01.00

Data: 01/04/2025

Regione Umbria

Guida Applicativa

Sommario

1. OBIETTIVO 4
2. FASCICOLO AZIENDALE 5
3. ANAGRAFICA 7
   3.1 Territorio 7
4. INTRODUZIONE 8
   4.1 Brevi annotazioni 8
5. MODULI E FUNZIONI 9
6. INSERIMENTO ANALISI DEL SUOLO 10
   6.1 Inserimento analisi del suolo valida per tutta l'azienda 10
   6.2 Inserimento analisi del suolo con riferimento catastale 10
7. PIANO DI CONCIMAZIONE 12
   7.1 Piano Concimazione SCHEDE Singola Azienda Singola Coltura 12
   7.2 Piano Concimazione SCHEDE Singola Azienda Multi-Coltura 14
8. MODULO MAGAZZINI MOVIMENTO PRODOTTI 17
   8.1 Rilievo giacenze iniziali – Carico senza documento 18
   8.2 Inserimento DDT e Fatture ricevute (acquisti) 19
9. MODULO QUADERNO DI CAMPAGNA 20
   9.1 Operazioni colturali 20
      9.1.1 Nuova Operazione 20
      9.1.2 Macchine e Operatori 22
      9.1.3 Note 23
      9.1.4 Concimazione Chimica 24
      9.1.5 Distribuzione Ammendanti Organici e Liquami 25
      9.1.6 Rilievo fioritura e fasi fenologiche 25
   9.2 Gestione trappole (Installazione e Reinnesco) 26
      9.2.1 Installazione trappole 26
      9.2.2 Reinnesco trappole 26
   9.3 Rilievo avversità 27
      9.3.1 Rilievi avversità nelle trappole 28
   9.4 Irrigazione 28
   9.5 Semina e Trapianto 29
   9.6 Rilievo produzione e data raccolta 30
   9.7 Lavorazioni e Altre lavorazioni 31
   9.8 Verifica conformità 31
10. STAMPA 33
   10.1 Scheda Biologico 33
   10.2 Schede materie prime 34
   10.3 Scheda Vendite
11. PROFITOSAN 37

1. OBIETTIVO

Il presente documento ha l'obiettivo di mostrare le funzionalità necessarie previste per adempiere alla compilazione dei procedimenti relativi alle domande BIO sulla piattaforma GARI.

2. FASCICOLO AZIENDALE

Cliccare su **Fascicolo** - **Fascicolo Aziendale**

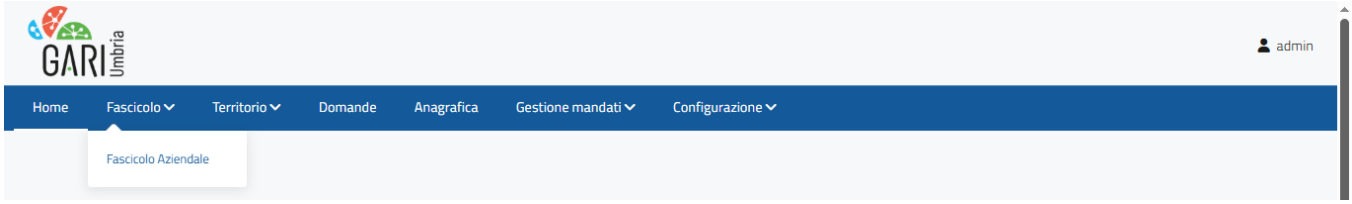

Cerca soggetto (Azienda Agricola) per CUAA o per Ragione Sociale.

Quindi cliccare sul **+** per selezionarla. In Tipo Fascicolo scegliere **Fascicolo Aziende Agricole**, quindi avviare la ricerca.

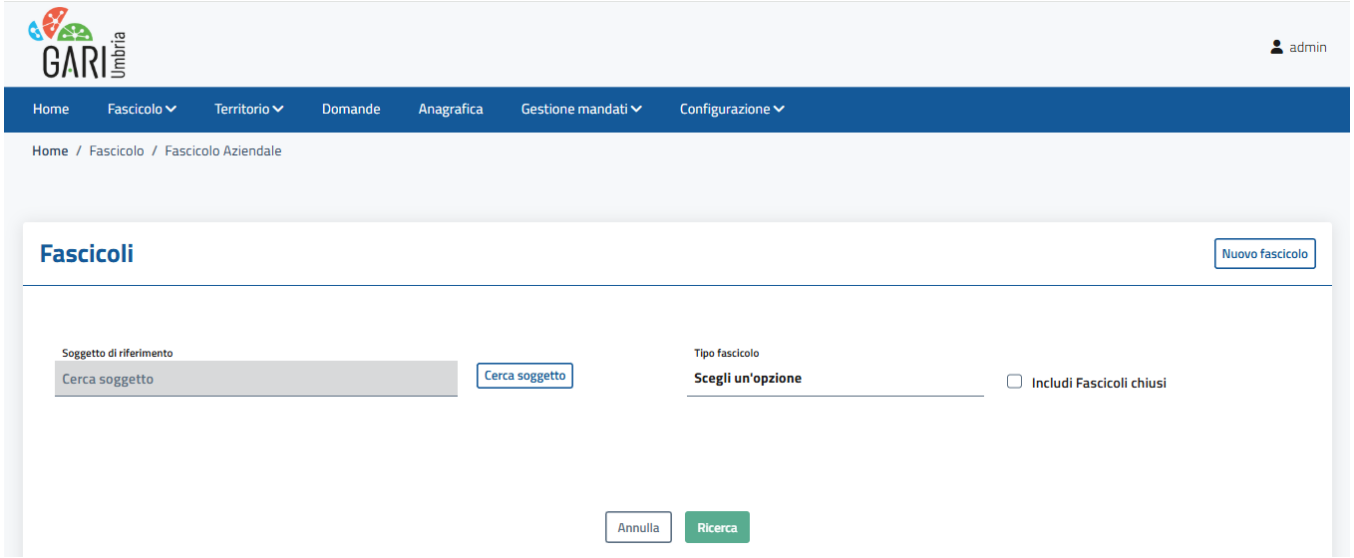

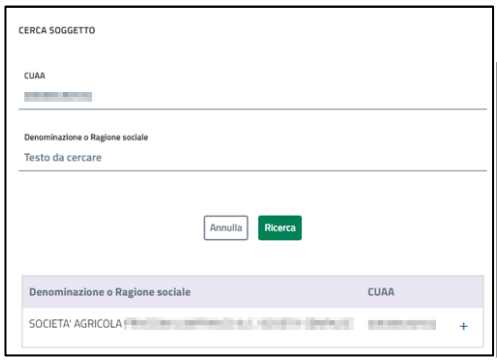

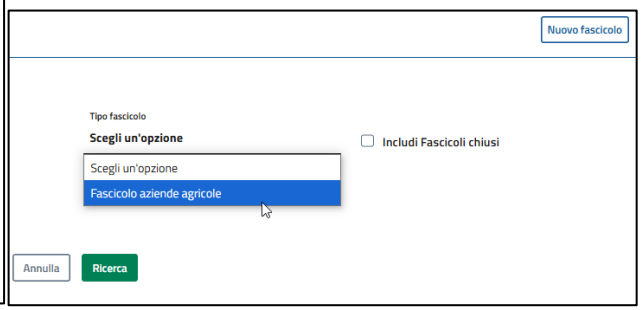

In Lista Fascicoli si trova l'elenco dei fascicoli aziendali, con il loro Stato ed il comando per l'accesso.

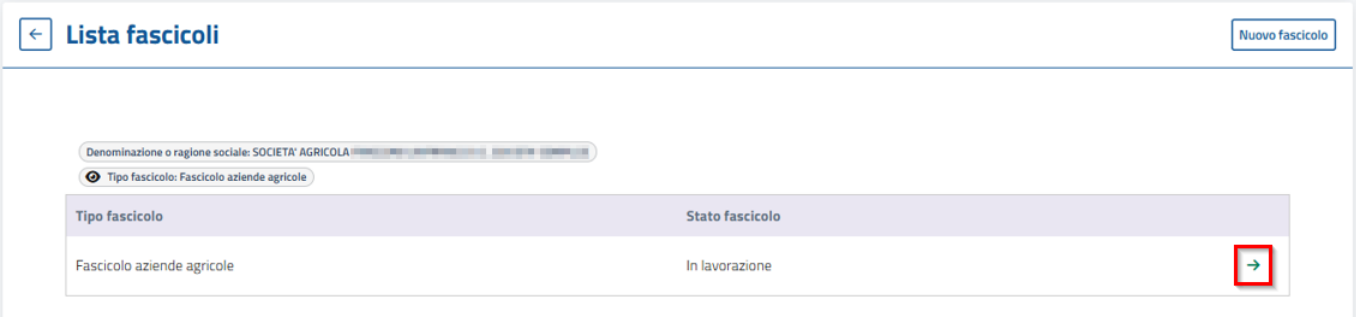

A sinistra l'elenco dei moduli a destra lo **Stato** del fascicolo ed il comando per registrare il **Passaggio di stato**

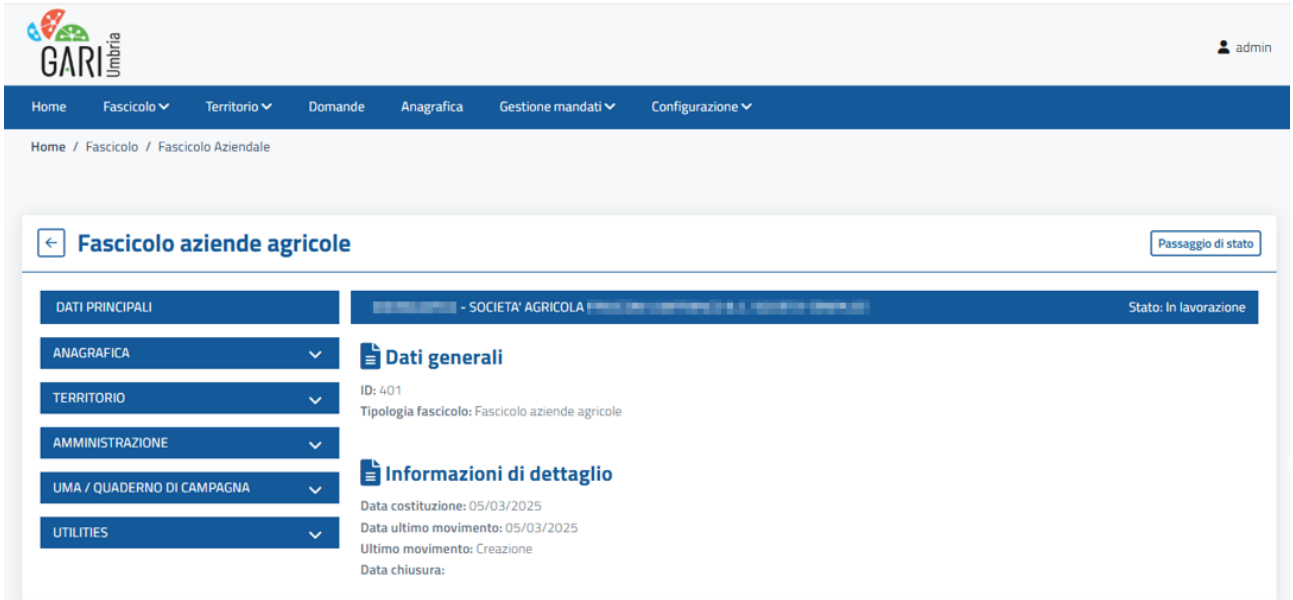

3. ANAGRAFICA

3.1 Territorio

Modulo in consultazione

Consistenza territoriale

Piano colturale

Importa – lancia il comando di scarico del piano colturale da AGEA

Apri Piano Colturale - Selezionare il Comune da consultare. I poligoni vengono riportati nella mappa centrale mentre l'elenco con tutte le informazioni è riportato sulla sinistra.

I dati sono solo in consultazione.

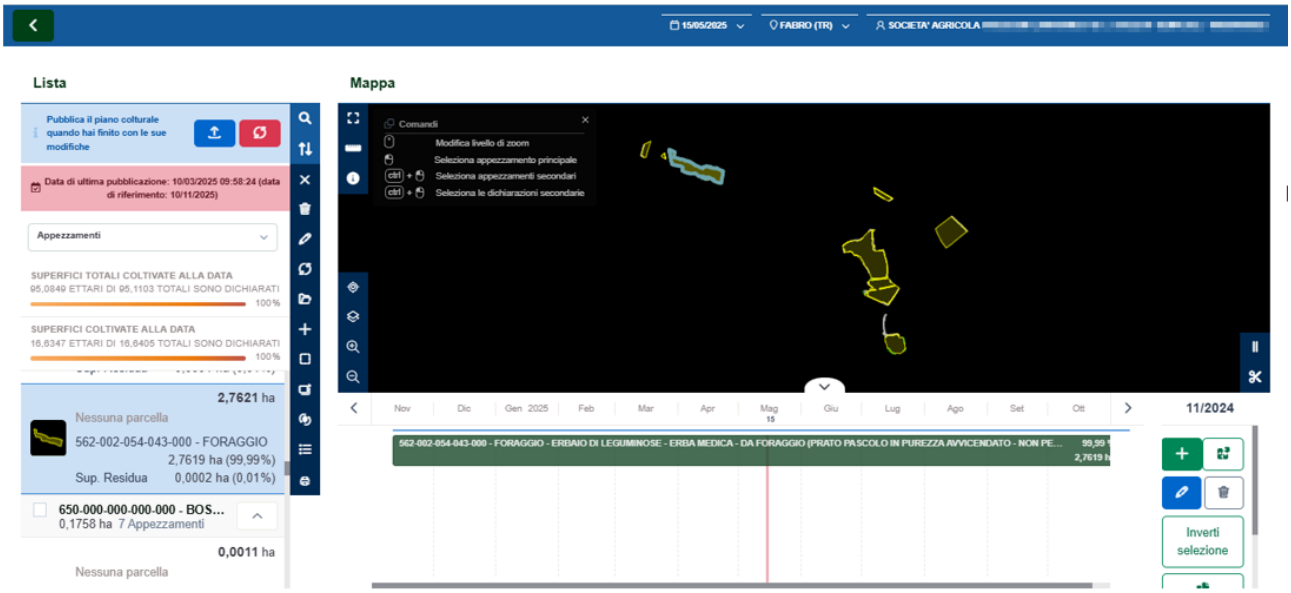

4. INTRODUZIONE

4.1 Brevi annotazioni

- Il programma è ottimizzato per Google Chrome;
- Al momento dell'accesso la prima schermata che compare è il Menù Principale.

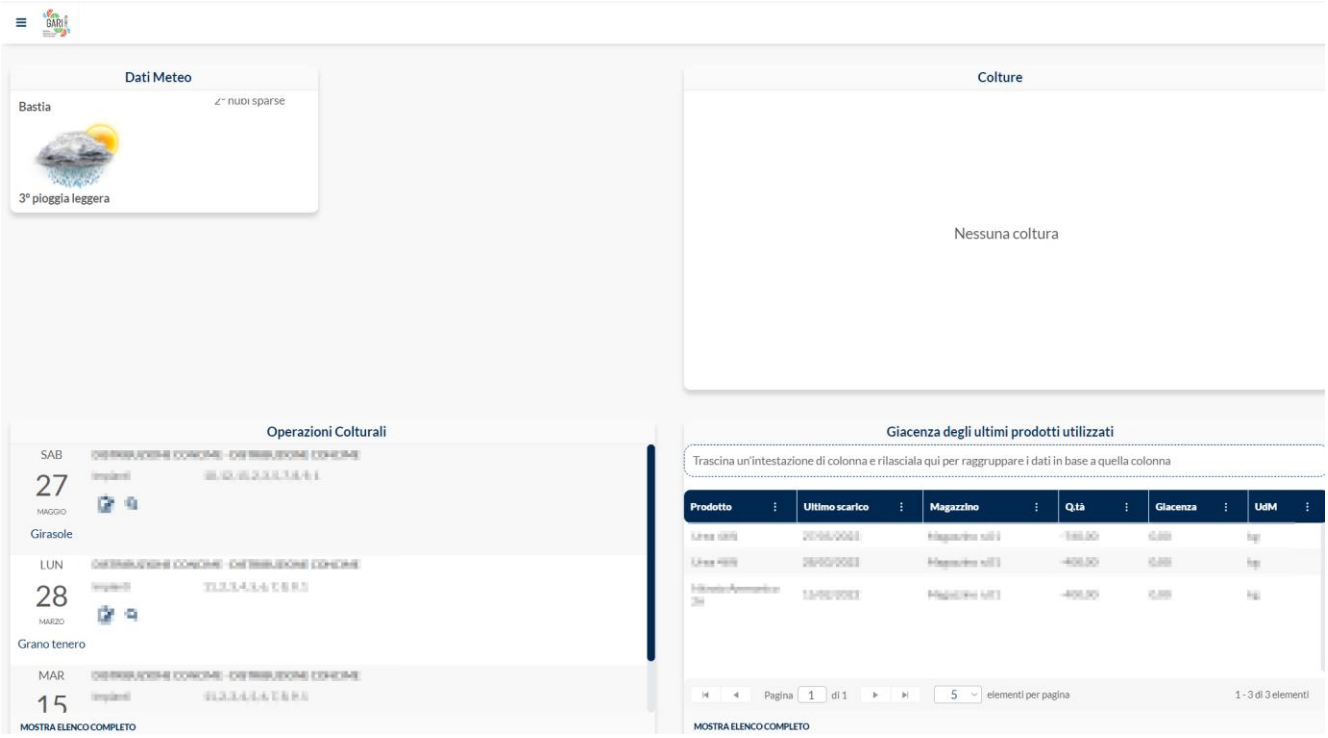

- Ricercare tramite filtro l'azienda da verificare prima di procedere
- Navigazione:

	Comando "Home" per tornare all'Homepage / Menù Principale.
	Comando "Indietro" per tornare alla pagina precedente.
	Comando "Burger-Menù" per aprire l'elenco delle Funzioni del Modulo in cui ci si trova.

5. MODULI E FUNZIONI

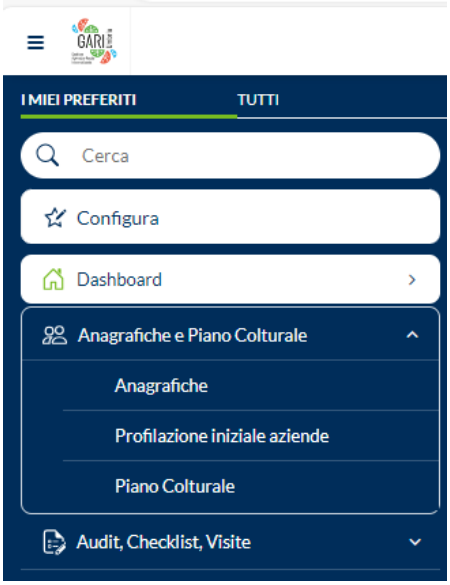

Il Burger - Menu è organizzato in Moduli e Funzioni secondo i permessi e le visibilità di cui dispone l'utente.

Aprendo con un click il Modulo (es: Anagrafiche e Piano Colturale), le Funzioni sono riportate sotto e facendo click sulla singola funzione si raggiunge la maschera utile.

Non ci sono ulteriori sottolivelli per raggiungere i contenuti funzionali del sistema.

Per impostare I MIEI PREFERITI: Aprire CONFIGURA, impostare su Personalizza, selezionare moduli o singole funzioni, click su CONFERMA.

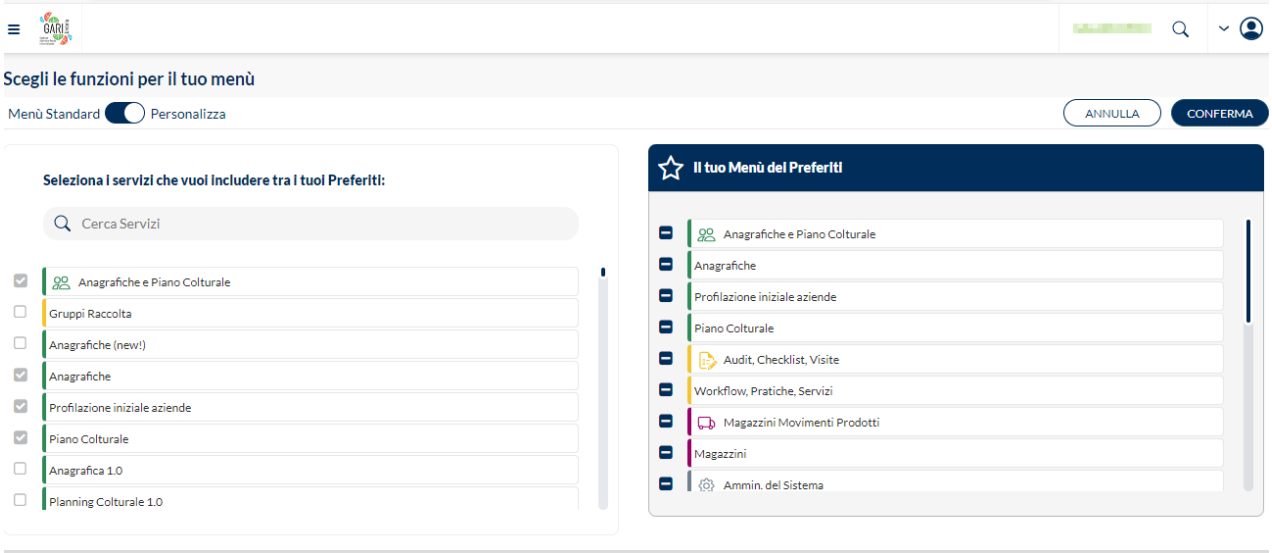

6. INSERIMENTO ANALISI DEL SUOLO

Modulo **Quaderno di Campagna**, Funzione **Piano di Concimazione**

Se per l'azienda non sono presenti dentro al programma Analisi del suolo, possono essere inserite e salvate manualmente dall'utente e richiamate in seguito per la compilazione del piano di concimazione.

L'analisi può essere unica per tutta l'azienda oppure essere riferita ad una o più particelle catastali.

6.1 Inserimento analisi del suolo valida per tutta l'azienda

Entrare in Nuovo - SCHEDE Singola Azienda Singola Coltura.

Selezionare NESSUNA ANALISI ed inserire i valori conosciuti facendo attenzione a FOSFORO E POTASSIO (nei riquadri rossi) per i quali è possibile scegliere la forma chimica di inserimento (P2O5/P – K2O/K).

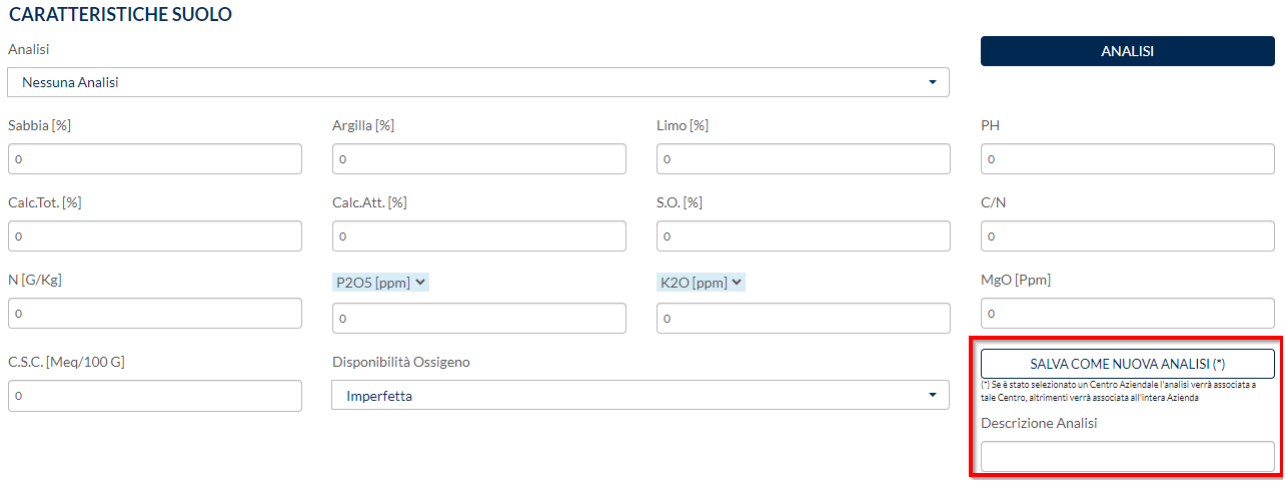

Al termine dell'inserimento riportare nel riquadro DESCRIZIONE ANALISI una denominazione di riferimento e SALVARE.

Non avendo dato alcun riferimento catastale, l'analisi sarà valida per tutta la superficie aziendale e selezionabile dal menù a tendina ANALISI.

6.2 Inserimento analisi del suolo con riferimento catastale

Per gestire le analisi con riferimento catastale, cliccare sul tasto blu ANALISI.

Nella pagina di gestione delle analisi del suolo seguire la seguente procedura: **1** – selezionare l'impresa, **2** – cliccare su foglio bianco (nuovo elemento),

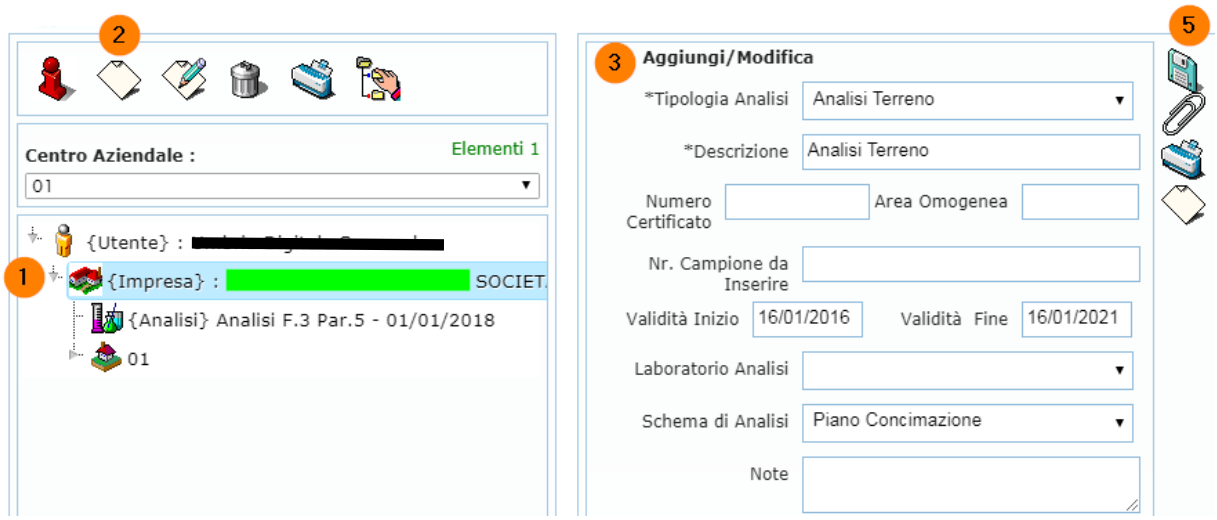

3 – compilare i campi con i dati conosciuti: tipologia analisi, descrizione, numero certificato, validità analisi (inizio e fine), laboratorio e schema di analisi (piano di concimazione) così da avere già in evidenza i parametri da inserire.

4 – inserire i valori conosciuti secondo le unità di misura riportate, **5** – salvare cliccando sul dischetto.

Dopo aver salvato è possibile allegare il documento di analisi in formato pdf richiamando il documento da SCEGLI FILE e cliccando su AGGIUNGI.

Procedura per associare l'analisi già inserita ad una o più particelle catastali:

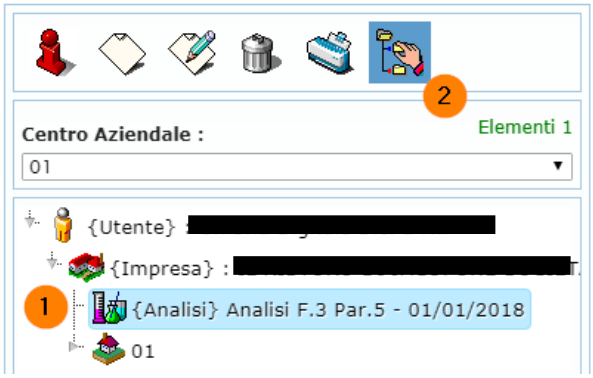

1 – selezionare l'analisi,

2 – cliccare sull'icona con la mano.

Nell'albero gerarchico i vari elementi diventeranno selezionabili.

3 - Aprire il centro, il catasto aziendale e selezionare le righe in base al foglio e particella interessati dall'analisi,

4 – confermare l'associazione con PROSEGUI OPERAZIONE.

NB: per associare l'analisi ad un'ulteriore particella catastale, bisogna selezionare tutte le particelle di competenza dell'analisi.

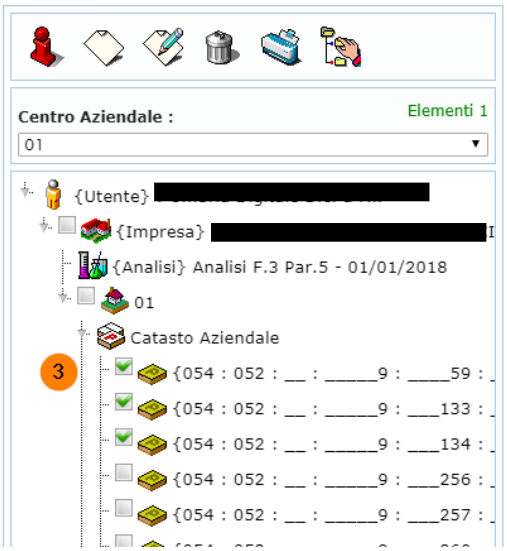

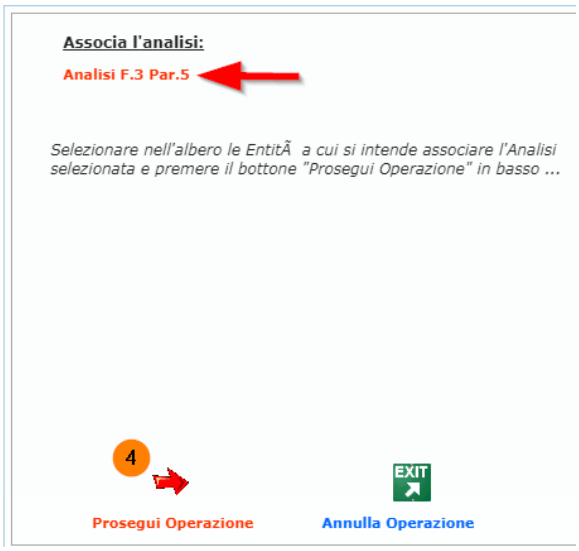

7. PIANO DI CONCIMAZIONE

Modulo **Quaderno di Campagna**, Funzione **Piano di Concimazione**

La pagina elenca i piani di concimazione dell'azienda con indicazione sulla validità, Regolamento, specie, tipologia (Bilancio o Schede) ed eventuale Dichiarazione di non concimazione.

Per ogni piano compilato ci sono i comandi di: lettura, modifica, cancellazione e stampa. Le icone indicano se al piano è collegato o meno l'allegato della stampa.

Per procedere alla compilazione cliccare su **NUOVO** e selezionare il metodo di calcolo:

Metodo bilancio previsionale: definire un piano di fertilizzazione sulla base di una serie di valutazioni analitiche (asportazioni, dotazione del suolo, perdite tecniche inevitabili per percolazione d'evaporazione, avvicendamento colturale, tecniche di coltivazione, etc.).

Metodo schede a dose standard: partendo dalla dose standard, intesa come la dose di NPK da prendere a riferimento in condizione ritenute ordinarie di fertilità del suolo, condizioni climatiche e resa produttiva, è possibile applicare delle modifiche in funzione delle situazioni individuate all'interno della scheda di fertilizzazione intese come INCREMENTI e DECREMENTI.

7.1 Piano Concimazione SCHEDE Singola Azienda Singola Coltura

NUOVO - SCHEDE Singola Azienda Singola Coltura.

Per redigere un piano di concimazione a schede lavorando a singola coltura utilizzando una singola analisi del suolo.

1 – selezionare il regolamento e le date di riferimento per la validità del piano;

DESCRIZIONE è un campo di testo libero (es: riferimento all'appezzamento e/o all'analisi del suolo); Dichiarazione di Non Utilizzo Fertilizzanti

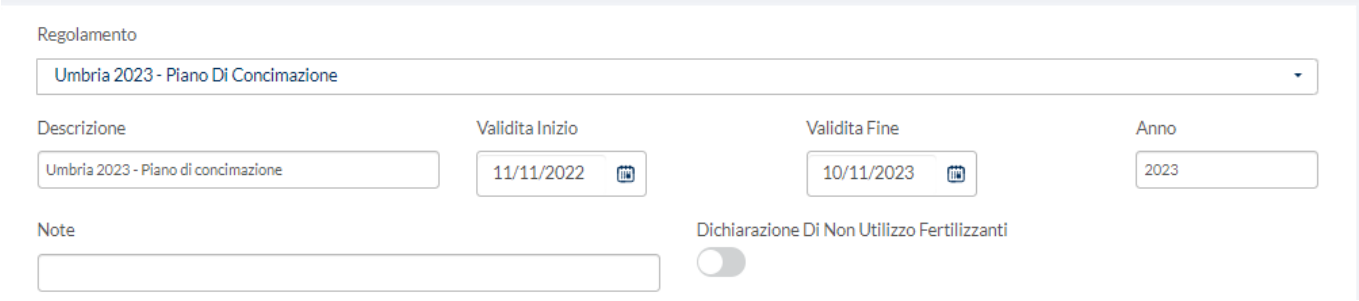

2 – selezionare la coltura ed inserire i dati ad essa riferiti (finalità, fase/ciclo, resa, etc.)

Per visualizzare solo le specie vegetali presenti nel Piano Colturale reso effettivo, mettere la spunta come in figura.

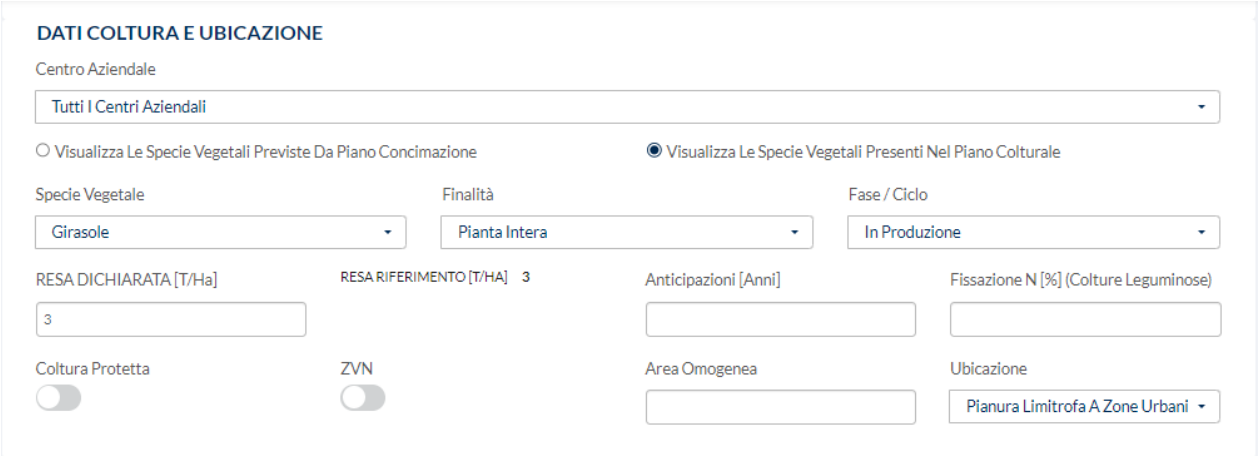

3 – selezionare dal menù a tendina l'analisi del suolo, i campi si popoleranno con i dati dell'analisi scelta.

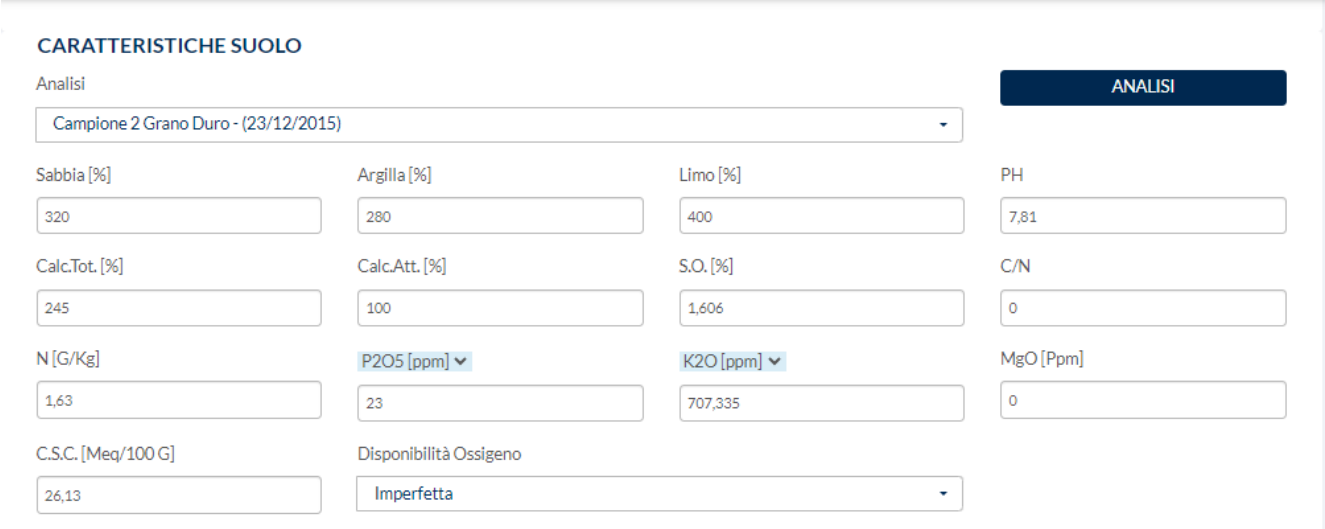

Per l'inserimento di una nuova analisi si rimanda al capitolo 1.

4 – inserire, se a disposizione, le informazioni sulle pratiche agronomiche ed i dati meteo relativamente alle precipitazioni del periodo autunno invernale (01/10 – 31/01) e le precipitazioni di febbraio.

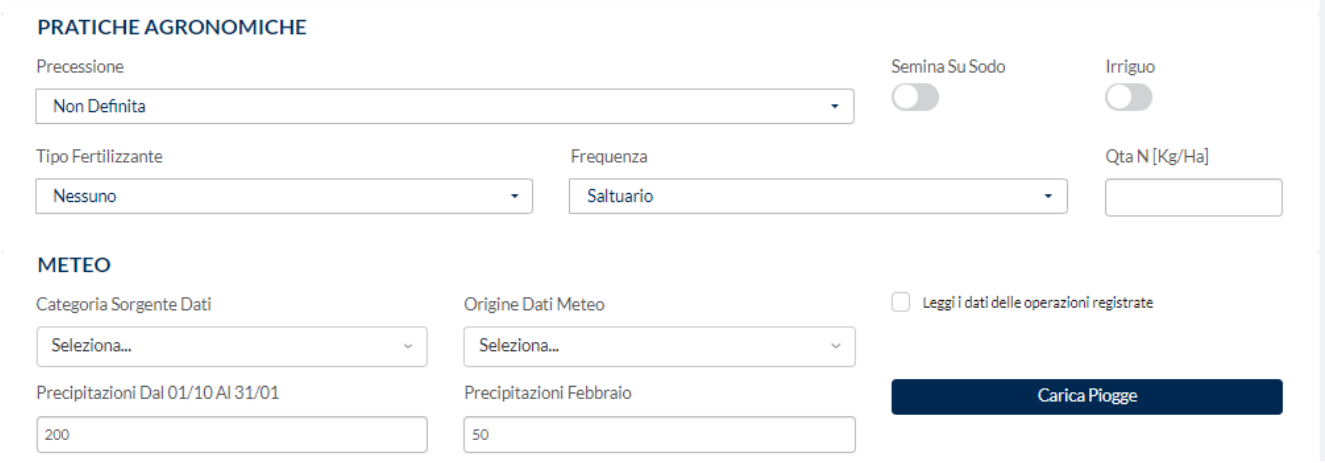

Al termine dell'inserimento dati avviare la procedura di calcolo, cliccando su CALCOLA BILANCIO.

La dose ricalcolata per Azoto, Fosforo e Potassio riporta i dettagli di incremento e decremento che possono essere modificati manualmente dall'operatore mettendo o togliendo la spunta sui singoli fattori correttivi.

AZOTO

	DECREMENTI	VALORE
☐	Resa bassa inferiore a 2,4	25
☐	Ammendante nell'anno precedente	20
☐	Tenore SO nel suolo elevato	20
☐	Dopo una leguminosa	40
☐	I anno di succ. a medica o prato > 5 anni	30
☐	II anno di succ. a medica o prato > 5 anni	50

	INCREMENTI	VALORE
☐	Resa alta superiore a 3,6	25
☑	Tenore SO nel suolo basso	20
☐	Lisciviazione x surplus pluviometrico	15
☐	Ristoppio o interramento paglie	30

Dose standard : 90
Limite MAS
Piano Concimazione: 130
Max Incrementi : 40
Totale incrementi : 20
Totale decrementi : 0
Dose ricalcolata : 110

FOSFORO

	DECREMENTI	VALORE
☐	Resa bassa inferiore a 2,4	10

	INCREMENTI	VALORE
☐	Resa alta superiore a 3,6	10

Selezionare la dose
Bassa
Dose standard : 60
Totale incrementi : 0
Totale decrementi : 0
Dose ricalcolata : 60

POTASSIO

	DECREMENTI	VALORE
☐	Resa bassa inferiore a 2,4	20

	INCREMENTI	VALORE
☐	Resa alta superiore a 3,6	20

Selezionare la dose
Normale
Dose standard : 120
Totale incrementi : 0
Totale decrementi : 0
Dose ricalcolata : 120

SALVA PIANO DI CONCIMAZIONE quindi selezionare gli appezzamenti e confermare con **ASSOCIA PIANO COLTURALE.** I massimali saranno visibili nelle singole colonne **Qta Max (Kg/Ha)**.

APPEZZAMENTI

☐	Centro Aziendale	Campo	App.	Catasto	Descrizione	Sup. [ha]	Data Inizio Impianto	Data Fine Impianto	Qta N Max [Kg/Ha]	Qta P Max [Kg/Ha]	Qta K Max [Kg/Ha]
☑	01	[illegible]	Strada	[illegible]	Orzo - Altre - Trasformazione per uso alimentare	3,1221	11/11/2022	10/11/2023	120	60	0
☑	01	[illegible]	Pozzo	[illegible]	Orzo - Altre - Trasformazione per uso alimentare	1,6695	11/11/2022	10/11/2023	120	60	0

7.2 Piano Concimazione SCHEDE Singola Azienda Multi-Coltura

NUOVO - SCHEDE Singola Azienda Multi-Coltura.

Per redigere un piano di concimazione a schede lavorando contemporaneamente su più colture dell'azienda con singole analisi del suolo.

1 – selezionare il regolamento e le date di riferimento per la validità del piano.

DESCRIZIONE è un campo di testo libero.

2 – selezionare l'opzione di aggregazione appezzamenti (riquadro rosso) per gestire "temporaneamente" come blocco unico gli appezzamenti con caratteristiche comuni in funzione del piano di concimazione.

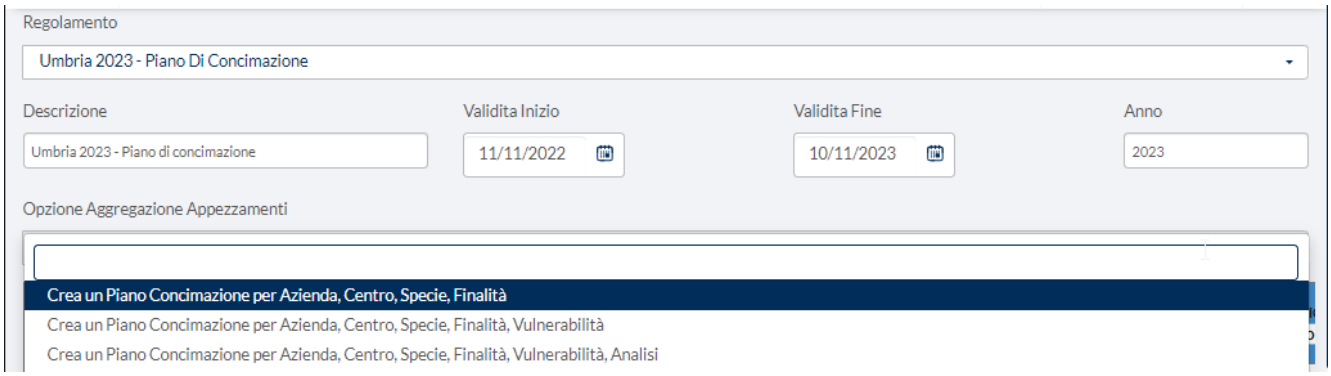

Sono possibili 3 livelli di aggregazione:

- **Specie e finalità produttiva**. Es: un appezzamento con tutta la superficie a vite – vinificazione; ed un appezzamento con tutta la superficie vite – da tavola).
- **Specie, finalità produttiva e vulnerabilità**. Vengono distinti se ricadono in zone vulnerabili o zone ordinarie (es: vite – vinificazione – ZVN; vite – vinificazione – ZO).
- **Specie, finalità produttiva, vulnerabilità ed analisi**. Vengono aggregati in base alle analisi del suolo associate al catasto (es: vite – vinificazione – ZVN – analisi 1; vite – vinificazione – ZVN – analisi 2).

Ricordo che le particelle catastali che ricadono in zone ZVN riportano l'indicazione **(V)**.

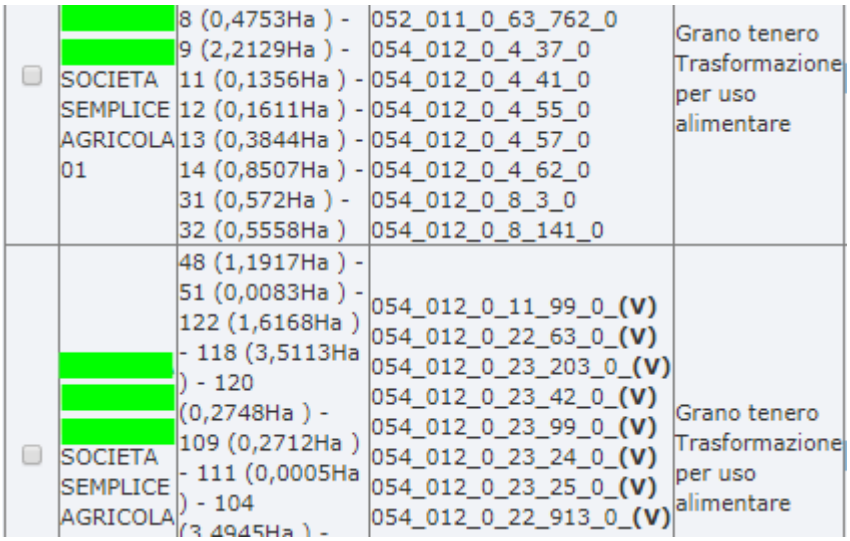

☐	SOCIETA SEMPLICE AGRICOLA 01	8 (0,4753Ha) - 9 (2,2129Ha) - 11 (0,1356Ha) - 12 (0,1611Ha) - 13 (0,3844Ha) - 14 (0,8507Ha) - 31 (0,572Ha) - 32 (0,5558Ha)	052_011_0_63_762_0 054_012_0_4_37_0 054_012_0_4_41_0 054_012_0_4_55_0 054_012_0_4_57_0 054_012_0_4_62_0 054_012_0_8_3_0 054_012_0_8_141_0	Grano tenero Trasformazione per uso alimentare
☐	SOCIETA SEMPLICE AGRICOLA	48 (1,1917Ha) - 51 (0,0083Ha) - 122 (1,6168Ha) - 118 (3,5113Ha) - 120 (0,2748Ha) - 109 (0,2712Ha) - 111 (0,0005Ha) - 104 (3,4945Ha) -	054_012_0_11_99_0_**(V)** 054_012_0_22_63_0_**(V)** 054_012_0_23_203_0_**(V)** 054_012_0_23_42_0_**(V)** 054_012_0_23_99_0_**(V)** 054_012_0_23_24_0_**(V)** 054_012_0_23_25_0_**(V)** 054_012_0_22_913_0_**(V)**	Grano tenero Trasformazione per uso alimentare

3 – Compilare la tabella in base alle infomazioni che si conoscono. Sono riportate le stesse informazioni del piano di concimazione per singola coltura: **Dati coltura e ubicazione**, **Pratiche agronomiche**, **Meteo**.

La riga in blu permette l'inserimento multiplo del dato su tutte le righe sottostanti. La stessa funzione multipla è per la selezione delle righe (freccia rossa).

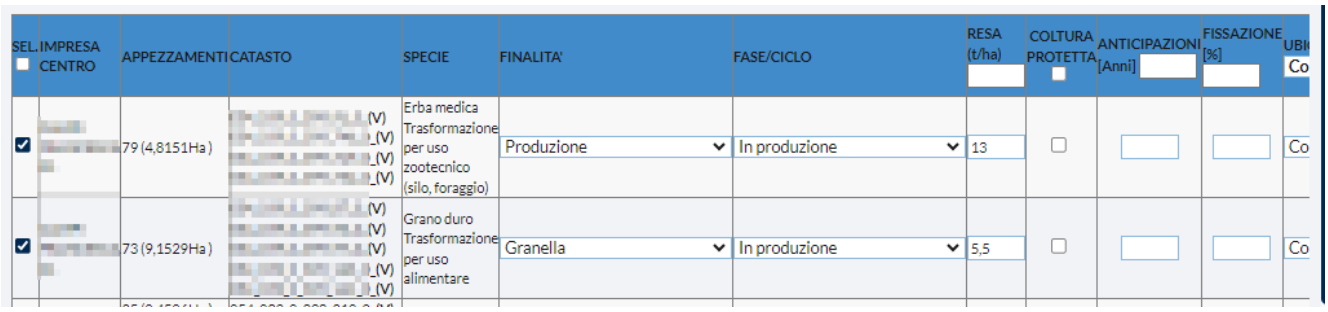

SEL.	IMPRESA CENTRO	APPEZZAMENTI	CATASTO	SPECIE	FINALITA'	FASE/CICLO	RESA (t/ha)	COLTURA PROTETTA	ANTICIPAZIONI [Anni]	FISSAZIONE [%]	UBI Co
☑		79 (4,8151Ha)	(V) (V) (V) (V)	Erba medica Trasformazione per uso zootecnico (silo, foraggio)	Produzione	In produzione	13	☐			Co
☑		73 (9,1529Ha)	(V) (V) (V) (V) (V)	Grano duro Trasformazione per uso alimentare	Granella	In produzione	5,5	☐			Co

Terminata la compilazione selezionare le righe per le quali si vuole procedere con il calcolo del Piano di concimazione e cliccare su **CALCOLA BILANCIO**.

CALCOLA BILANCIO

Il risultato del calcolo è presentato in griglia.

SEL ✓	IMPRESA	IMPIANTI	SPECIE	FINALITÀ	N AMMESSO [KG/HA]	P AMMESSO [KG/HA]	K AMMESSO [KG/HA]	DETTAGLIO	N DA ASSEGNARE AGLI APPEZZAMENTI [KG/HA]	P_AMMESSO DA ASSEGNARE AGLI APPEZZAMENTI [KG/HA]	K AMMESSO DA ASSEGNARE AGLI APPEZZAMENTI [KG/HA]
☑	[illegible]	79 (4,8151Ha)	Erba medica Trasformazione per uso zootecnico (silo, foraggio)	Produzione	0	0	0	Dettaglio	0	0	0
☑	[illegible]	73 (9,1529Ha)	Grano duro Trasformazione per uso alimentare	Granella	160	15	10	Dettaglio	160	15	10

DETTAGLIO per consultare e modificare i singoli piani di concimazione: Analisi del suolo e Dose standard (incrementi/decrementi).

Se sono state apportate modifiche ai valori di analisi del suolo procedere con **RICALCOLA BILANCIO** e successivamente **AGGIORNA BILANCIO**; Se la modifica ha riguardato solamente i fattori correttivi, è sufficiente l'AGGIORNA BILANCIO.

ANNULLA | RICALCOLA BILANCIO | AGGIORNA BILANCIO

Completare la procedura selezionando i piani che vogliono essere salvati ed associati agli appezzamenti.

8. MODULO MAGAZZINI MOVIMENTO PRODOTTI

Filtro di ricerca sulla destra della pagina. Scegliere tra la visualizzazione delle consistenze di magazzino ad una determinata data inserita nel campo **Giacenza al giorno**

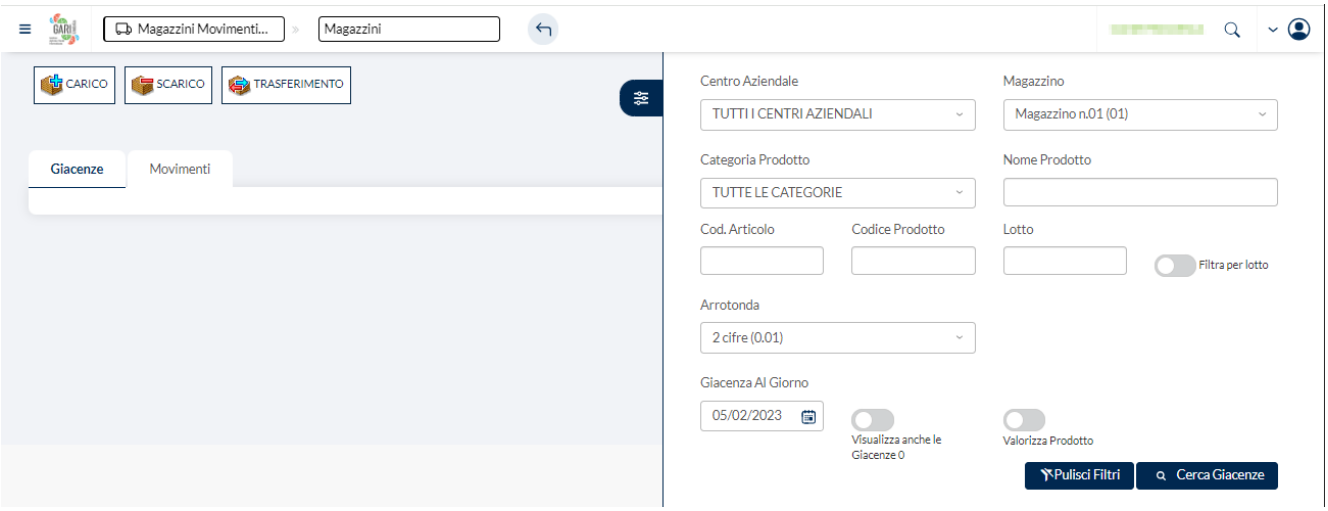

O visualizzare i movimenti di magazzino impostando il periodo di tempo (**dal – al**) che si vuole interrogare.

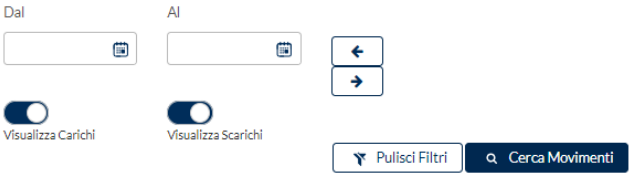

La griglia mostra la quantità di prodotto presente ed il dettaglio del movimento di entrata/uscita in **Descrizione Attività**.

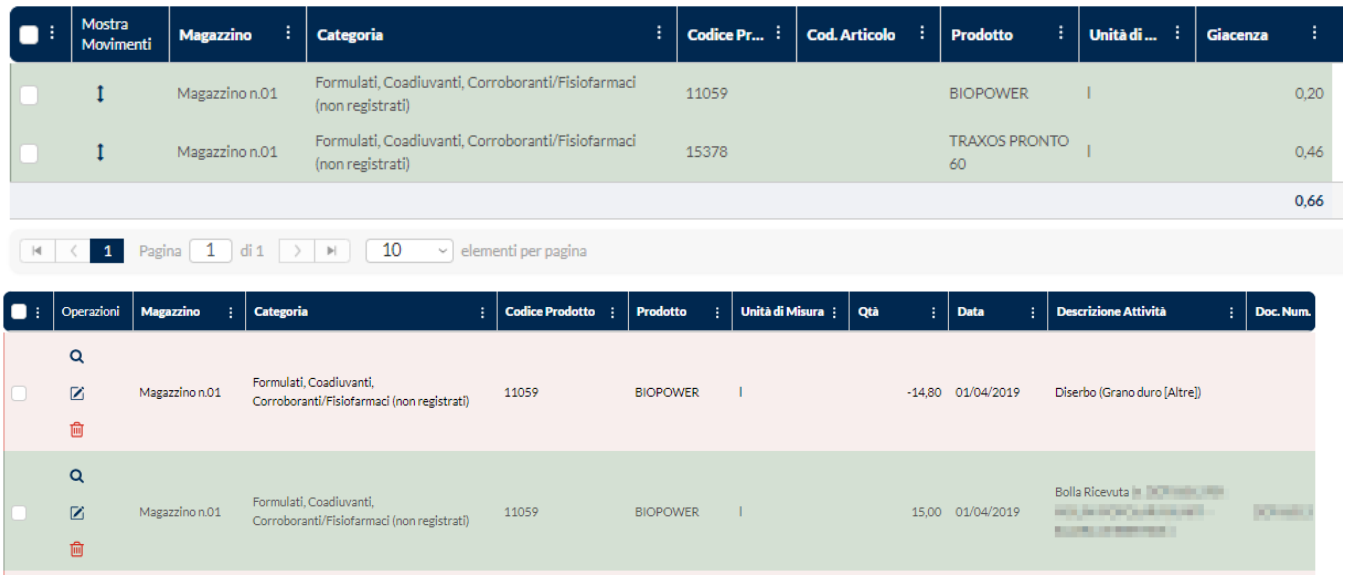

Mostra Movimenti	Magazzino	Categoria	Codice Pr...	Cod. Articolo	Prodotto	Unità di ...	Giacenza
	Magazzino n.01	Formulati, Coadiuvanti, Corroboranti/Fisiofarmaci (non registrati)	11059		BIOPOWER	l	0,20
	Magazzino n.01	Formulati, Coadiuvanti, Corroboranti/Fisiofarmaci (non registrati)	15378		TRAXOS PRONTO 60	l	0,46
							0,66

1 Pagina 1 di 1 10 elementi per pagina

Operazioni	Magazzino	Categoria	Codice Prodotto	Prodotto	Unità di Misura	Qtà	Data	Descrizione Attività	Doc. Num.
	Magazzino n.01	Formulati, Coadiuvanti, Corroboranti/Fisiofarmaci (non registrati)	11059	BIOPOWER	l	-14,80	01/04/2019	Diserbo (Grano duro [Altre])	
	Magazzino n.01	Formulati, Coadiuvanti, Corroboranti/Fisiofarmaci (non registrati)	11059	BIOPOWER	l	15,00	01/04/2019	Bolla Ricevuta	

8.1 Rilievo giacenze iniziali – Carico senza documento

Per creare un'operazione di carico di prodotto senza documento (es: inserire l'inventario di fine anno) l'operazione è **CARICO.**

Inserire la data di carico, selezionare la causale ed il magazzino di destinazione.

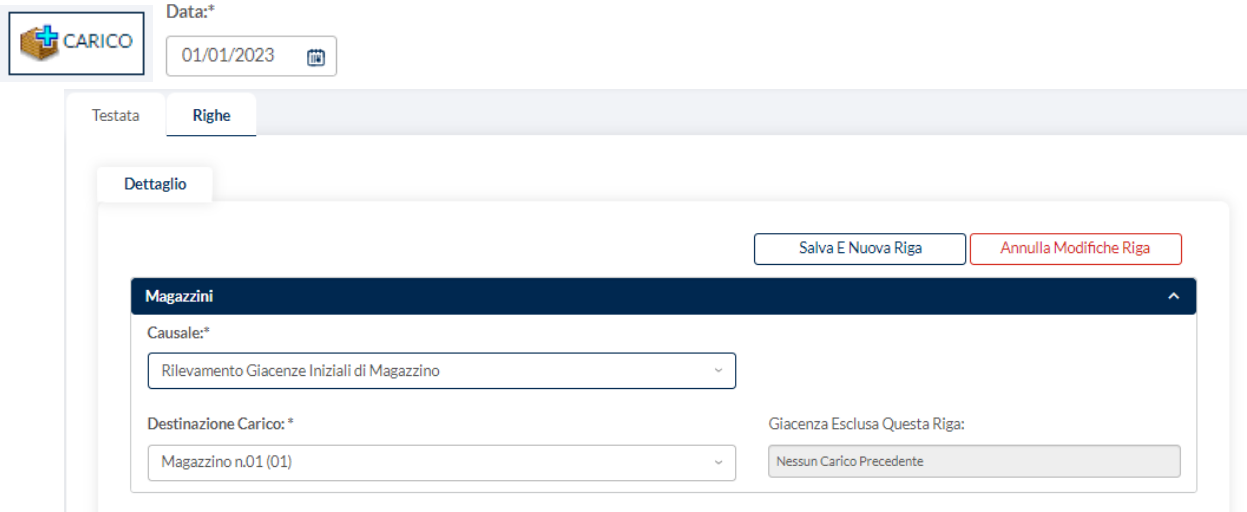

Per effettuare la ricerca prodotto, scegliere la categoria e scrivere parte del nome (almeno 3 caratteri). Selezionare il prodotto, inserire la quantità.

Salva E Nuova Riga per caricare altri prodotti anche cambiando la categoria qualora fosse diversa (es: fertilizzanti, semente e materiale vivaistico, trappole commerciali, etc.).

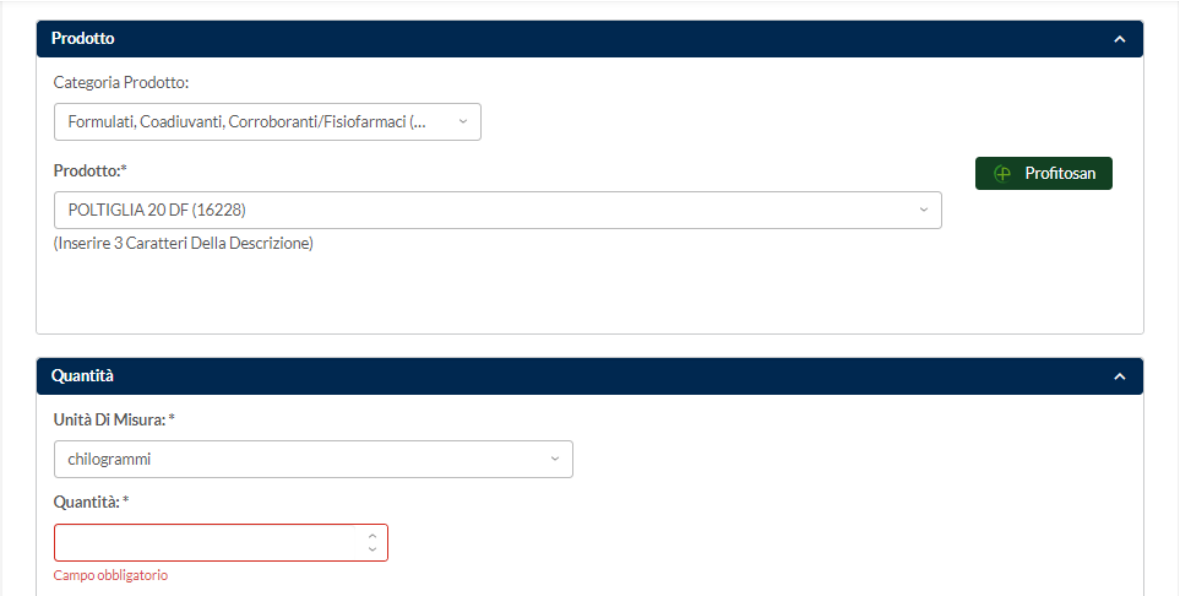

Per chiudere l'operazione

NB: per i **fertilizzanti organici** (es: Reflui zootecnici, Digestati, etc.) inserire la Direttiva Nitrati.

8.2 Inserimento DDT e Fatture ricevute (acquisti)

Modulo **Acquisti**, Funzione **DDT Ricevuti**

Inserire il numero documento (sono presenti anche i campi per il prefisso e suffisso), la data emissione documento e ricercare il fornitore inserendo una parte del nome.

Se mancante il fornitore può essere inserto direttamente con il pulsante che riporta l'icona **+**

I passaggi successivi sono i medesimi del carico: scelta del magazzino di destinazione, categoria e prodotto, quantitativo e salvataggio.

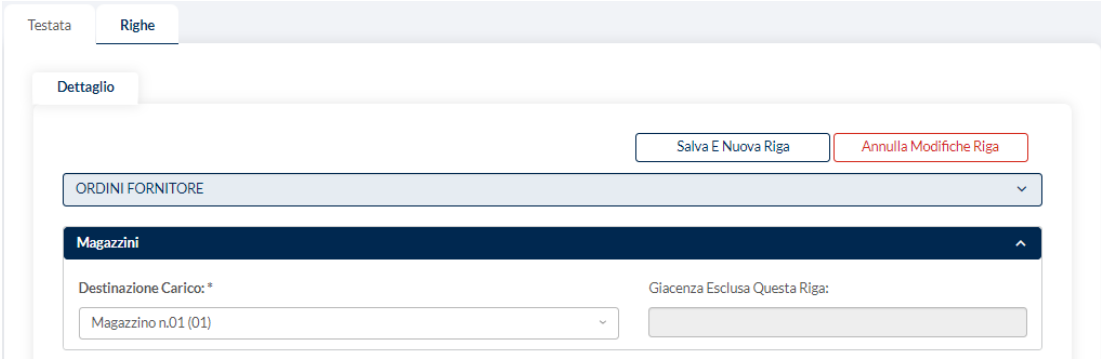

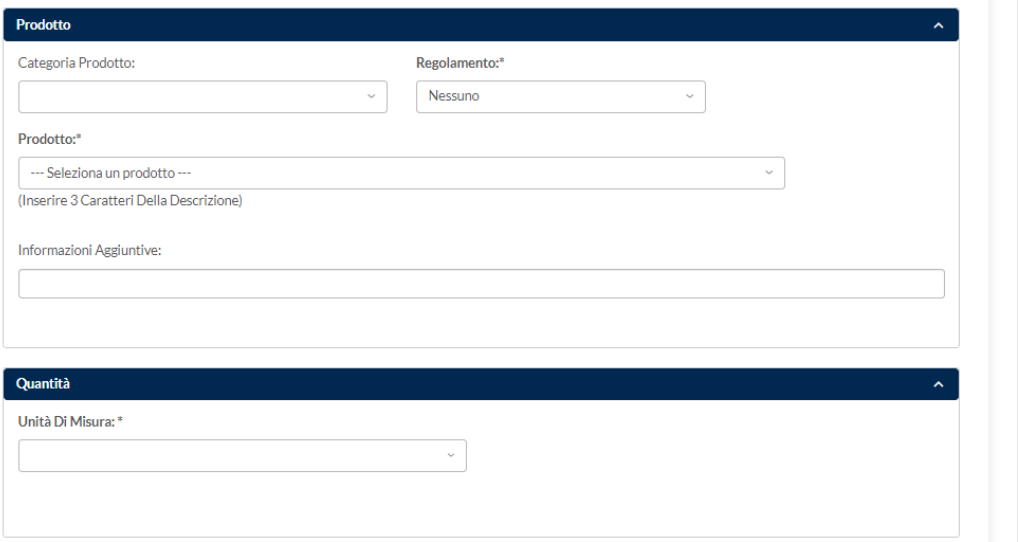

NB: per i **fertilizzanti organici** (es: Reflui zootecnici, Digestati, etc.) inserire la Direttiva Nitrati.

Al temine del salvataggio DDT, il documento inserito verrà aggiunto all'elenco dei documenti già presenti che possono essere riaperti in modifica/lettura/stampa.

9. MODULO QUADERNO DI CAMPAGNA

9.1 Operazioni colturali

Modulo **Quaderno di Campagna**, Funzione **Operazioni Colturali**

La griglia riporta tutte le operazioni registrate sull'azienda. Il filtro temporale è nella linguetta sulla destra. Sopra la griglia sono riportati i comandi principali: Copia operazioni, Stampa, Verifica conformità, Modifica multipla operazioni, nuova operazione.

Ogni singola operazione può essere aperta in modifica e in lettura.

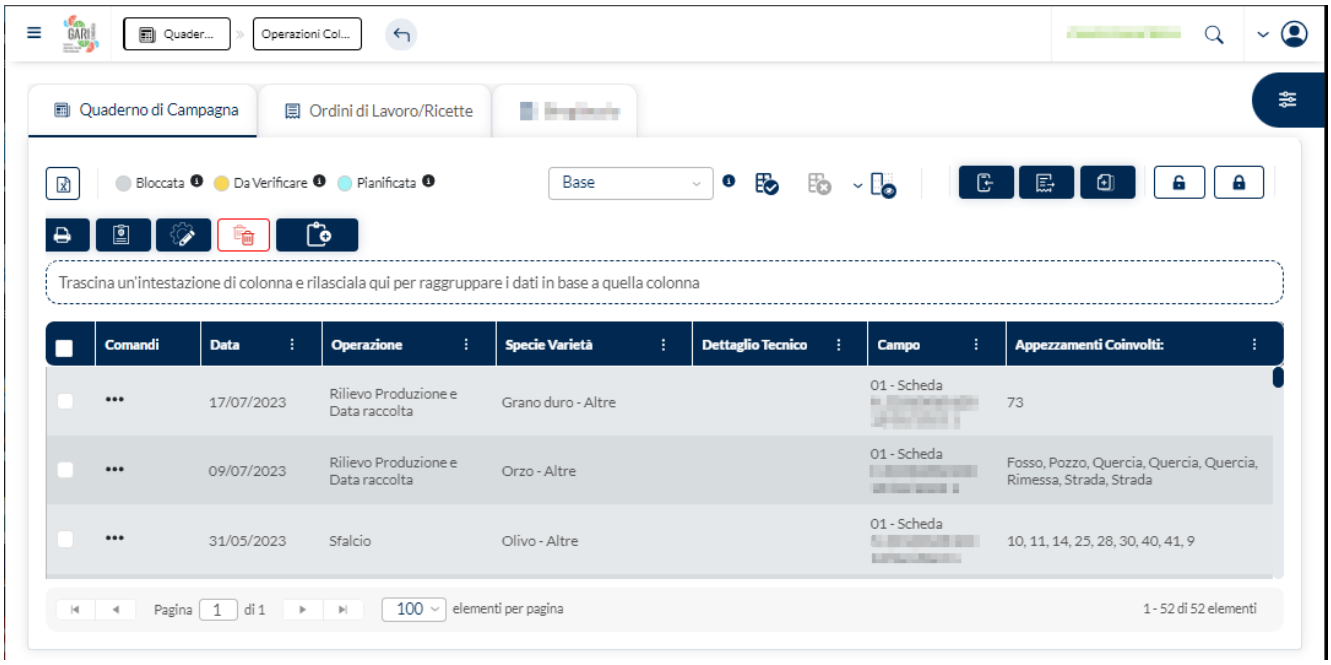

9.1.1 Nuova Operazione

il comando è unico. All'apertura della pagina inserire Data, Specie e Operazione Colturale

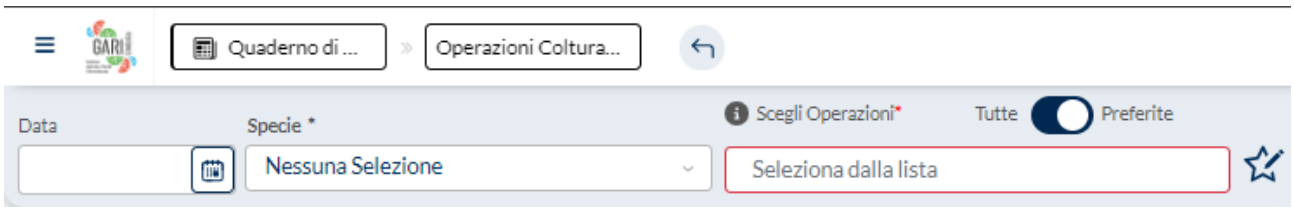

È possibile inserire più di un'operazione colturale compatibile (es: Trattamento antiparassitario + Concimazione fogliare).

Dalla griglia IMPIANTI selezionare gli appezzamenti coinvolti nell'operazione ed eventualmente inserire per ogni singola riga nella colonna **Sup.Trattata [Ha]**, la riduzione di superficie. Il totale della superficie trattata è riportato in fondo alla pagina e su quella si basano i calcoli e controlli dei dosaggi a ettaro.

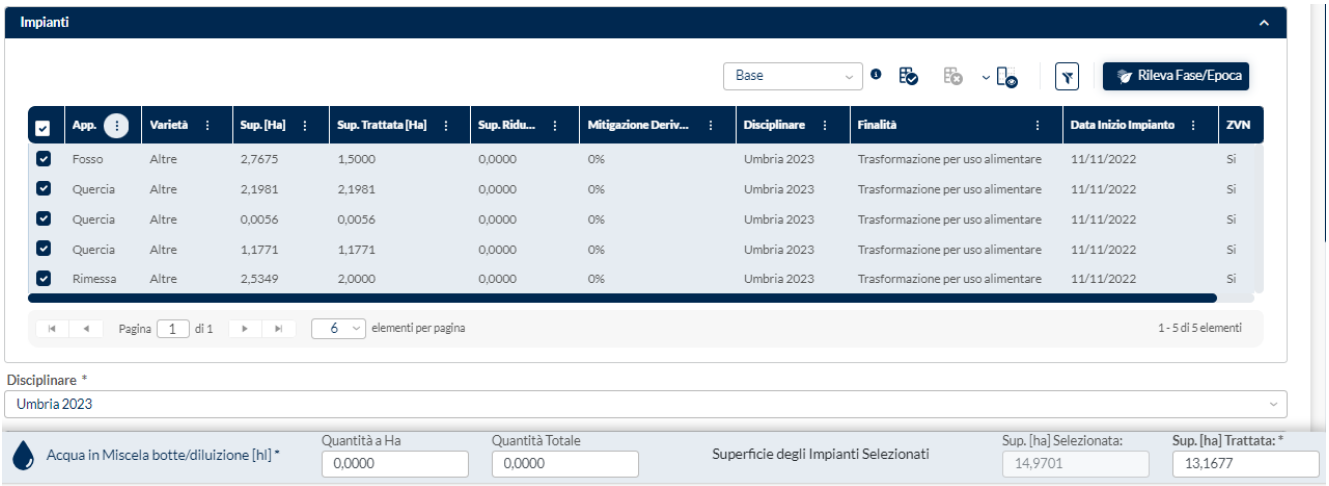

Se l'impianto ha anche la dicitura **superficie contigua a corpi idrici** accompagnata da un valore ed è stato selezionato un prodotto che riporta in etichetta l'indicazione Buffer Zone, il programma calcola e riduce in automatico la superficie che non deve essere trattata riportando il valore nella colonna **Sup.Riduzione[Ha]Buffer**.

Se l'azienda adotta metodi che diminuiscono l'effetto deriva (ugelli antideriva etc.), è possibile indicare la percentuale nella specifica colonna **Mitigazione Deriva [%]** ed il valore Buffer verrà opportunamente ridotto.

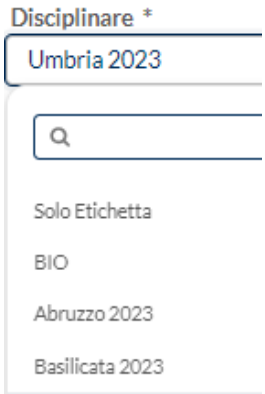

Nel riquadro Disciplinare (campo obbligatorio), viene impostato il livello di controllo dell'operazione: Solo Etichetta, BIO o DPI regionale.In questo caso :BIO

Il vincolo può essere preimpostato sia a livello di utente che di singola Azienda e/o singolo impianto.

La ricerca prodotto parte con il click su l'icona con blu con la lente: può essere generale su tutte le giacenze a magazzino o puntuale inserendo parte del nome del prodotto.

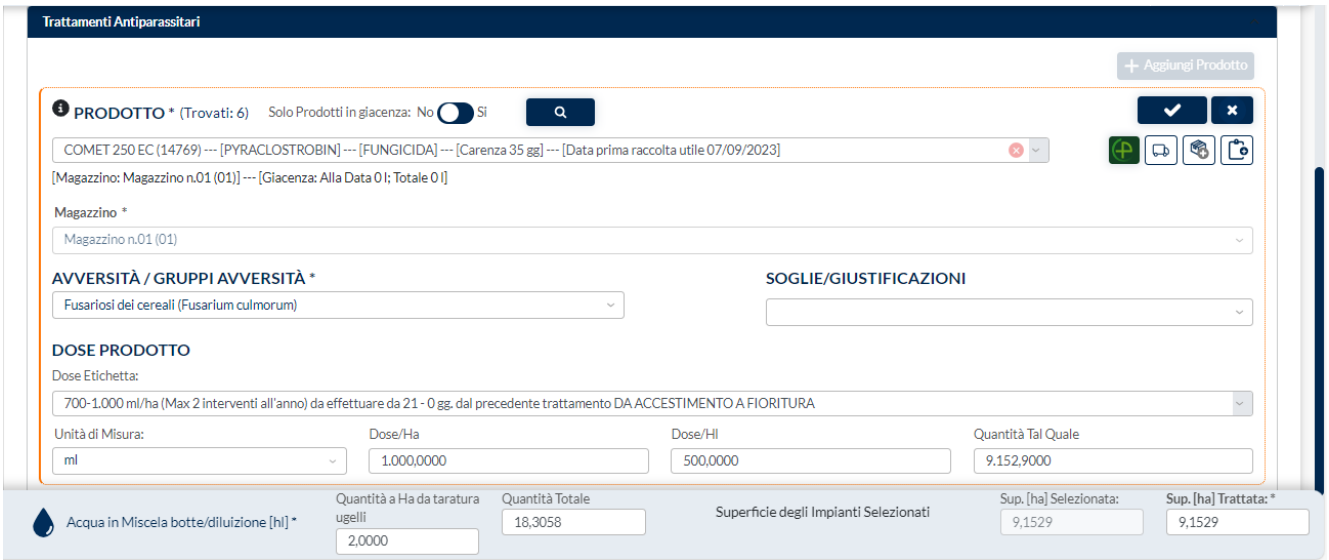

Le icone a destra della cella prodotto sono: collegamento con la scheda prodotto, visualizzazione movimenti di magazzino, carico di magazzino, Nuovo DDT ricevuto.

Dopo aver selezionato il prodotto procedere con il selezionare **Avversità/Gruppi Avversità** (per i bagnanti non comparirà), eventuali **Soglie/Giustificazioni** di intervento e **Dose Prodotto** negli appositi campi.

Inserire **l'Acqua in Miscela botte/diluizione** espressa come ettolitri (Hl) a ettaro o totali e specificare la dose di prodotto effettivamente utilizzata, riferita a **Dose/Ha**, **Dose/Hl** o **Quantità Tal Quale**.

Sempre a destra della cella prodotto ci sono le icone:

per confermare o annullare il dato prodotto inserito.

le icone diventano di modifica o cancellazione, una volta salvato il dato prodotto.

per inserire un altro prodotto fitosanitario alla miscela, fare click sull'icona e ripetere la procedura precedentemente descritta da ricerca prodotto fitosanitario.

In alto a destra della pagina ci sono i comandi per la verifica ed il salvataggio dell'intera operazione.

Salva e Nuovo – per inserire un altro trattamento

Salva e duplica – per copiare gli stessi dati ad una nuova data da inserire.

Salva ed Esci – per tornare alla griglia riepilogativa.

9.1.2 Macchine e Operatori

Macchine e Operatori censiti per azienda (compresi i terzisti) possono essere associati all'operazione registrata:

Nuova Riga, nella colonna **Risorsa** cercare la macchina o l'operatore e con fermare la selezione con la spunta verde che comparirà.

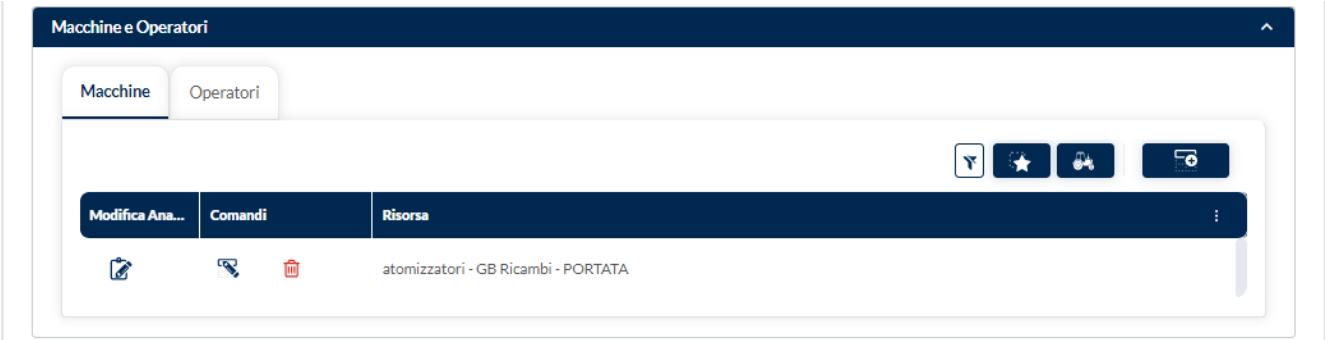

Possono essere inserite più righe sia per le macchine che per gli operatori ripetendo la procedura descritta.

Comando che permette di salvare la combinazione Macchina Operatore per le prossime operazioni.

Comandi che permettono di censire nuove risorse (Macchine e Operatori) in Anagrafica azienda. In rosso i campi da compilare per il salvataggio del dato.

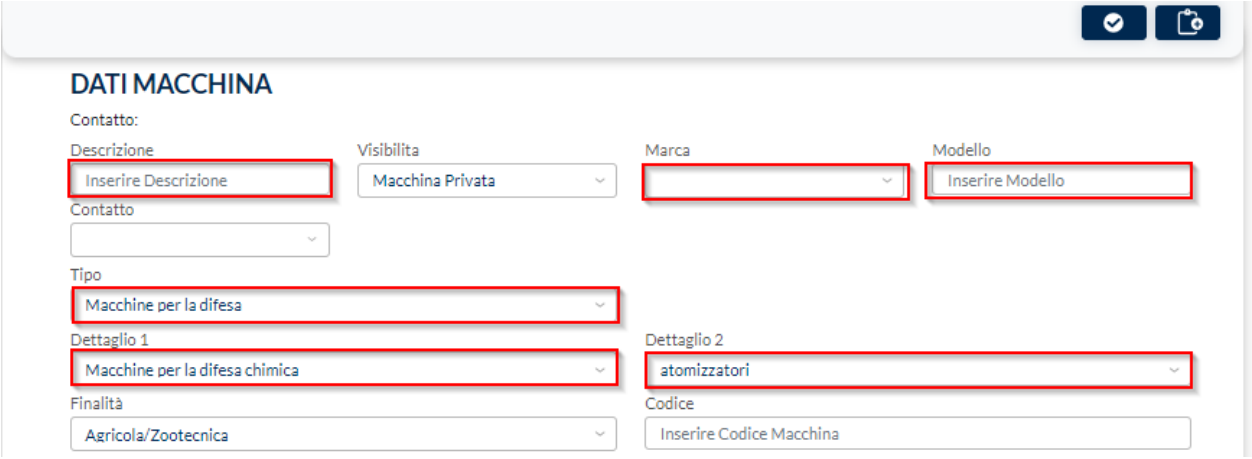

Per gli Operatori inserire il Rapporto Contabile ed i riferimenti del Patentino per l'utilizzo dei prodotti fitosanitari. Il tasto Salva è in alto a destra della pagina.

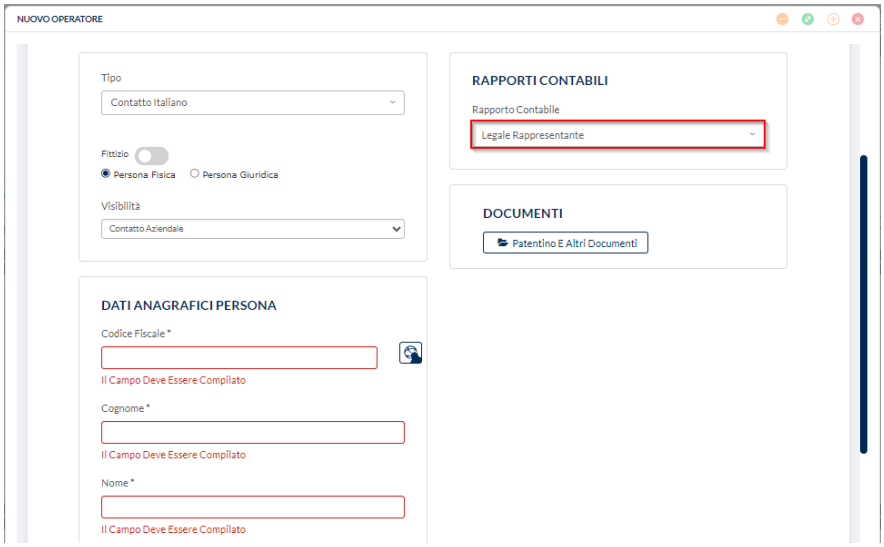

9.1.3 Note

Il campo Note si divide in: campo di testo libero e in Gruppi (**Giutificazioni tecniche** e **Meteo**) per le quali sono state preimpostate delle note che sono a selezione multipla.

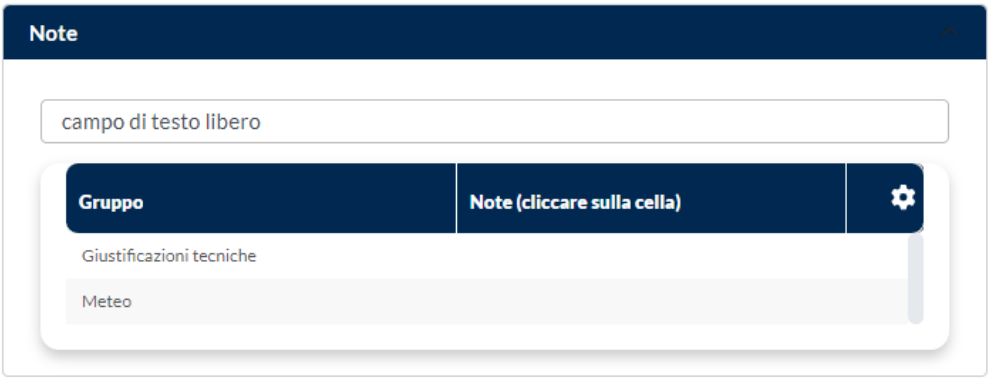

9.1.4 Concimazione Chimica

*Sono distinte quattro operazioni in base alla tipologia del prodotto (chimica/organica) ed alla modalità di distribuzione (con/senza ausilio di acqua):

- **Distribuzione Concime** = concimazione chimica a piano campo, senza uso di acqua (granulare)
- **Concimazione Fogliare** = concimazione chimica con acqua
- **Fertirrigazione** = concimazione chimica con acqua per mezzo di sistemi di fertirrigazione

*Nella griglia Impianti le colonne NPK e CU (rame) [Kg/Ha] riportano il valore **massimo** distribuibile durante l'anno, il **Già Distribuito** (espresso anche come %del totale) ed il **Residuo** distribuibile.

***Dose Consigliata,** sono le unità di NPK e Cu (rame) [Kg/Ha] distribuite per singola operazione.

L'informazione è completa con l'aggiornamento del residuo (unità di NPK e Cu ancora distribuibili) , potendo consultare anche i quantitativi distribuiti con le precedenti concimazioni.

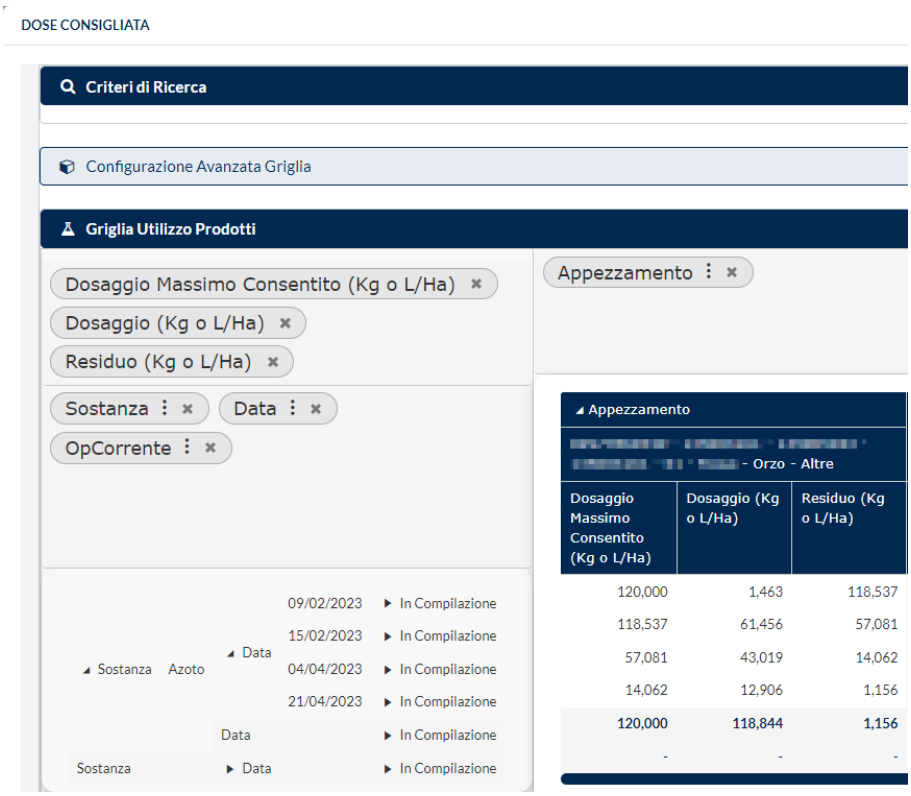

9.1.5 Distribuzione Ammendanti Organici e Liquami

L'operazione è legata alla **Direttiva Nitrati** regionale.

La DGR deve essere indicata insieme all'epoca/modalità di distribuzione prima della ricerca prodotto.

Questi parametri sono necessari per i coefficienti efficienza del calcolo dell'N Utile distribuito.

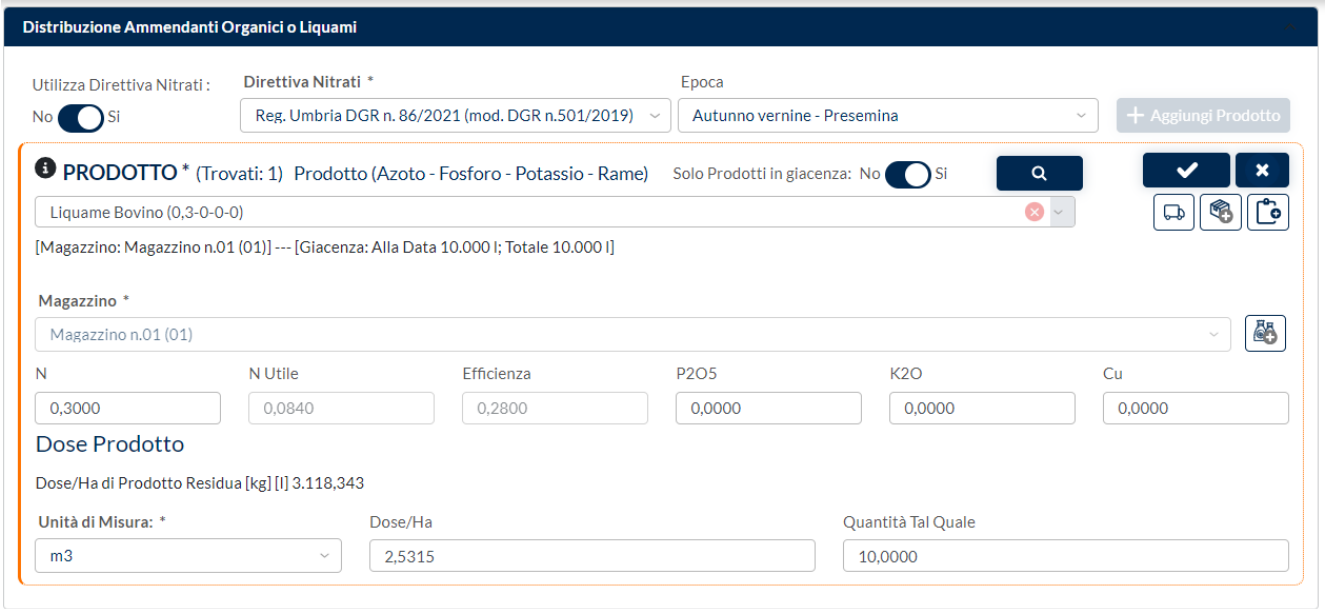

Per i concimi organici le singole caselle NPK sono editabili con i valori da analisi (come prevede la DGR).

Con il titolo inserito e con l'efficienza si ricava l'azoto utile che entra nel calcolo della dose consigliata.

9.1.6 Rilievo fioritura e fasi fenologiche

L'operazione può essere registrata direttamente dalla griglia IMPIANTI in ogni operazione con un click su

oppure registrando la singola operazione **Rilievo Fioritura/Fasi Fenologiche**.

Le fasi fenologiche sono riportate in elenco con la descrizione ed il codice BBCH.

Selezionare la fase, inserire la data di osservazione e confermare con Aggiunti.

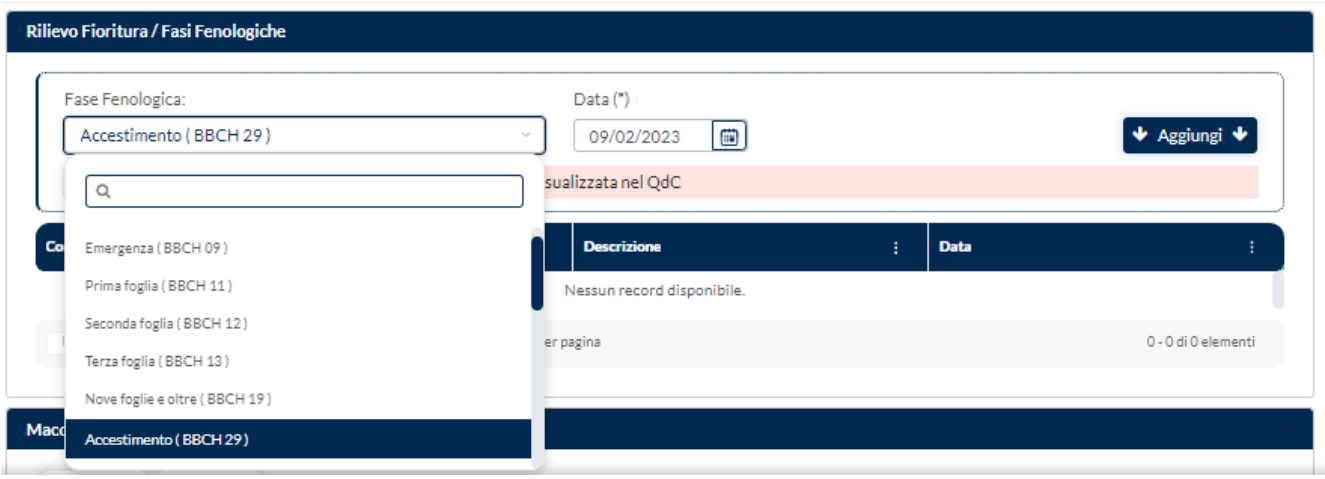

Ripetere l'operazione per aggiungere altre osservazioni fenologiche, il dato è modificabile per singola riga nella griglia di riepilogo sottostante.

9.2 Gestione trappole (Installazione e Reinnesco)

9.2.1 Installazione trappole

Campi obbligatori: **1** – data di installazione, **2** – specie vegetale e Centro Aziendale, **3** – provenienza risorse.

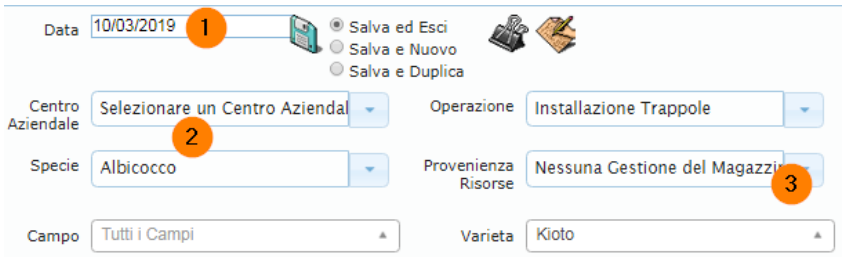

4 – selezionare gli impianti dove sono state installate le trappole.

5 – ricercare il prodotto dai menù **Dispenser** e **Avversità** ed inserire il numero totale di trappole installate.

6 – confermare i dati con la freccia rossa e gestite il posizionamento delle trappole (freccia rossa).

Con la griglia aperta salvare l'operazione con: **Salva ed Esci** – per tornare al menù agenda; **Salva e Nuovo** – per inserire un altro trattamento; **Salva e duplica** – per copiare gli stessi dati ad una nuova data da inserire.

9.2.2 Reinnesco trappole

La registrazione può essere fatta solo dopo aver registrato **Installazione Trappole.**

Inserire la data del reinnesco, richiamare le trappole installate inserendo: centro aziendale, specie e specificando la provenienza delle risorse. Cliccare sulla freccia rossa **Mostra le Trappole.**

Nella griglia **1** - selezionare le trappole da reinnescare e **2** – inserire il numero di inneschi utilizzati per trappola.

Con la griglia aperta salvare l'operazione con: **Salva ed Esci** – per tornare al menù agenda; **Salva e Nuovo** – per inserire un altro trattamento; **Salva e duplica** – per copiare gli stessi dati ad una nuova data da inserire.

9.3 Rilievo avversità

Nel menù agenda sono state distinte tre operazioni:

- **Rilievi avversità in campo** = presenza/assenza o percentuale dell'avversità o dei danni da avversità
- **Rilievi erbe infestanti** = presenza delle infestanti espressa come piante per metro quadro
- **Rilievi avversità nelle trappole** = numero di catture per trappola.

Il rilievo può essere inserito anche direttamente nella pagina Trattamento Antiparassitario – Diserbo. La registrazione deve essere con Disciplinare e con soglia di intervento.

Il tasto è a destra di **Soglie/Giustificazioni**

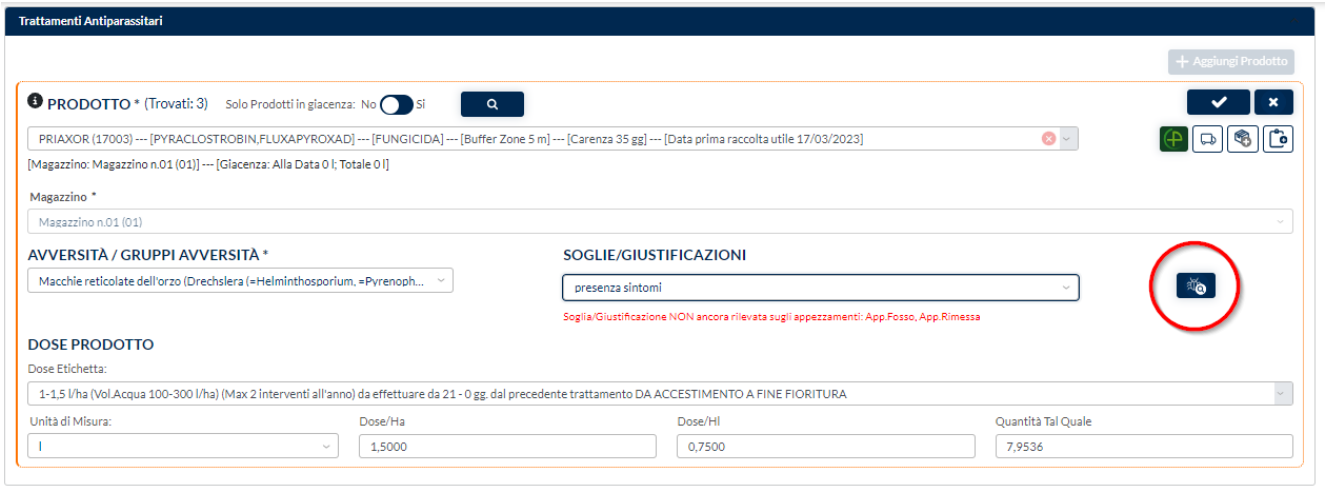

Dopo aver indicato la data e selezionato la superficie, ricercare l'avversità e scrivere la quantità rilevata. Confermare il dato inserito con **Aggiungi.** È possibile inserire più di un rilievo con avversità diverse.

L'unità di misura è riportata nella descrizione dell'avversità (se si tratta di presenza, inserire nella colonna **Q.tà** presenza = 1, assenza = 0).

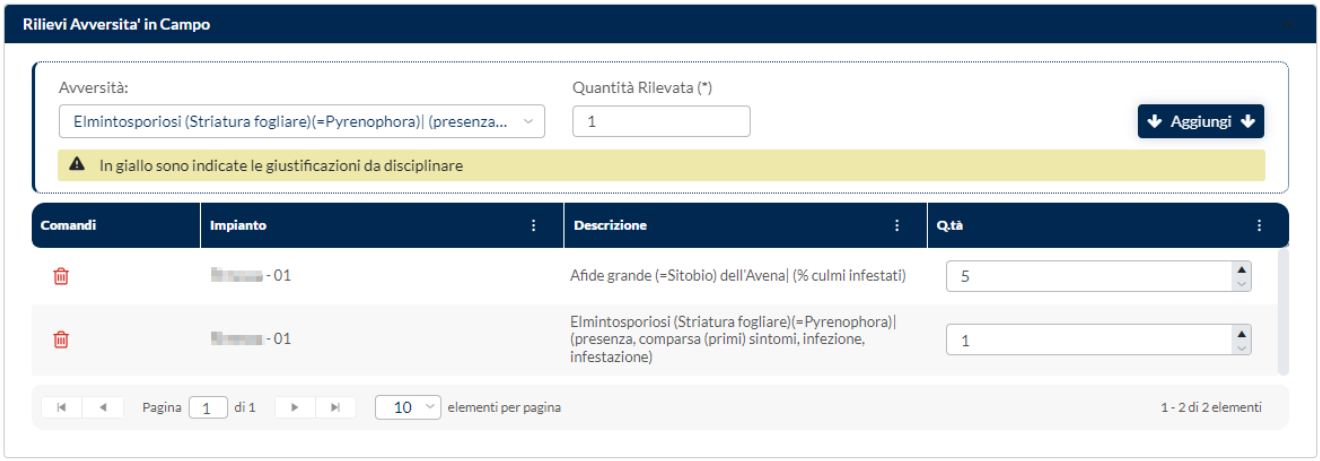

Nella griglia di riepilogo le singole informazioni possono essere modificate o cancellate.

9.3.1 Rilievi avversità nelle trappole

La registrazione può essere fatta solo dopo aver registrato **Installazione Trappole.**

Richiamare le trappole installate, inserendo: data del rilievo, centro aziendale e specie vegetale.



Click sulla freccia rossa Mostra le Trappole.

Nella griglia di riepilogo **4** – selezionare le trappole di cui si vuole inserire il rilievo, **5** – inserire il valore di cattura per singola trappola.

NB:
Situazione trappole al 02/04/2018
La colonna 'Inneschi Attivi' visualizza gli inneschi attivi alla data dell'operazione; vengono visualizzati solo gli ultimi reinneschi ed ignorati quelli precedenti
Sono visualizzate per il reinnesco le sole trappole installate nell'anno corrente.
Le righe in rosa indicano che gli inneschi sono scaduti alla data attuale

Indicare il numero di avversità rilevate nelle trappole

CENTRO AZIENDALE	SPECIE	VARIETÀ	APPEZZ. DI INSTALLAZIONE	CODICE TRAPPOLA	CODICE PERSONALE	DESCRIZIONE TRAPPOLA	AVVERSITA	USO TRAPPOLA	DATA INSTALLAZIONE	DATA ULTIMO INNESCO	SCADENZA	INNESCHI ATTIVI ALLA DATA OPERAZIONE	4	5 NUMERO AVVERSITÀ RILEVATE
Centro Prova	Albicocco	Altre	albicocco prova	1	0	Real control Mosca della frutta (monitor)	CERTCA	Installazione Trappole	02/04/2018		14/05/2018	1	☑	5
Centro Prova	Albicocco	Altre	albicocco prova	2	0	Real control Mosca della frutta (monitor)	CERTCA	Installazione Trappole	02/04/2018		14/05/2018	1	☑	2

Con la griglia aperta salvare l'operazione.

9.4 Irrigazione

Si può registrare un intervento irriguo singolo come l'insieme di interventi irrigui in un arco temporale.

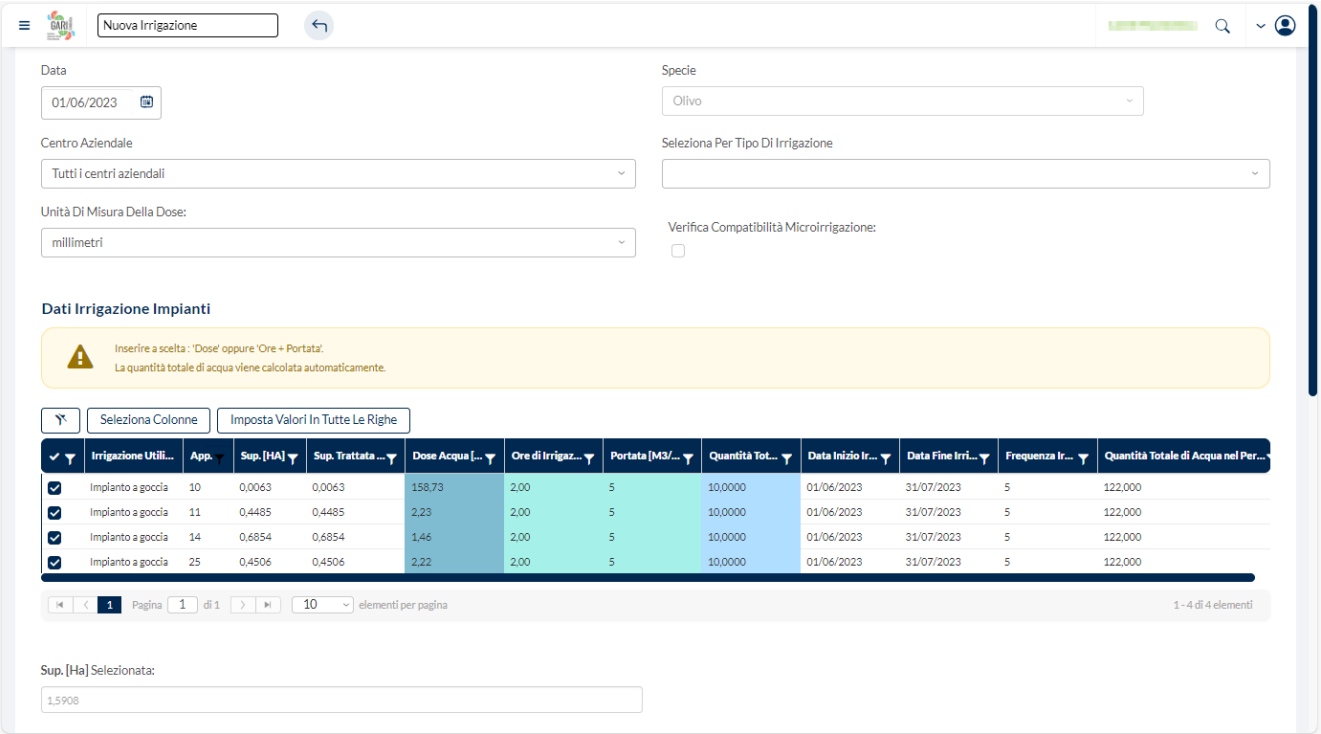

Scegliere **Unità di misura della Dose** che si vuole utilizzare nella griglia Dati Irrigazione Impianti.

I dati possono essere insieriti per singola riga oppure con **Imposta Valori In Tutte Le Righe** compilare in modo massivo tutta la griglia.

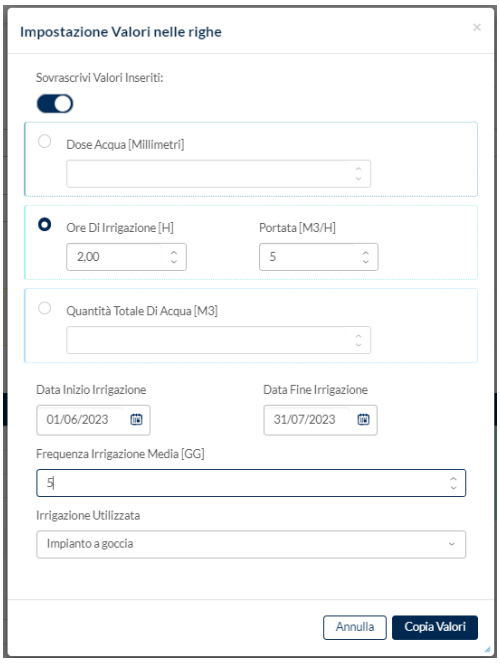

Scegliere il metodo di calcolo della **Quantità Totale di Acqua [M3]** per singolo intervento:

- **Dose acqua** (m^3/Ha) – compilando la colonna blu
- **Ore di Irrigazione** (H) x **Portata** (m^3/H) – compilando le colonne verdi.

Nelle colonne **Data Inizio/Fine irrigazione** inserire il periodo di adacquamento e nella colonna **Frequenza di Irrigazione Media [GG]** ogni quanti giorni si ripete l'operazione all'interno del periodo indicato, es: data inizio irrigazione: 01/06/2023 data fine irrigazione: 31/07/2023 frequenza irrigazione media: 5 = in un arco di tempo di 60 giorni, ogni 5 viene irrigato.

Nella colonna **Quantità Totale di Acqua nel Periodo [M3]** viene riportato l'intero quantitativo di acqua distrubuita nel periodo indicato.

9.5 Semina e Trapianto

Per la semina sono gestite anche altre due operazioni specifiche: **Semina per sovescio** e **Semina su sodo.**

Inserire la data e selezionare la superficie ricercando gli impianti come Specie o come Terreno Nudo – Uso agricolo da definire (es: nella gestione di un secondo raccolto).

Scegliere tra le opzioni di salvataggio proposte.

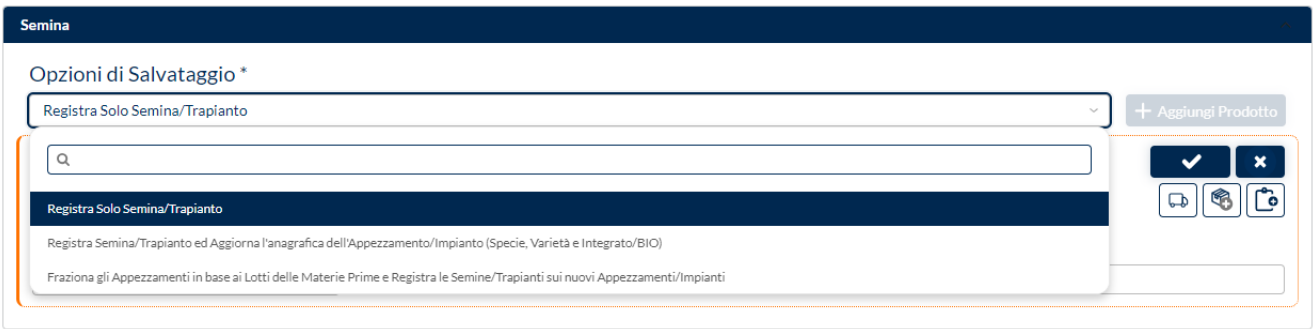

Opzioni Salvataggio:

- **Registra Solo Semina/Trapianto**: Registra solamente l'operazione lasciando invariati i dati anagrafici.
- **Registra Solo Semina/Trapianto ed Aggiorna l'anagrafica dell'Appezzamento/Impianto** (es: terreno nudo diventa impianto di pomodoro, nella gestione di un secondo raccolto).
-

Ricercare il prodotto caricato precedentemente a magazzino ed indicare la **Quantità Totale** utilizzata o la **Densità/Ha** di semina-trapianto (piante o semente /Ha).

9.6 Rilievo produzione e data raccolta

Inserire la data di inizio raccolta, la specie e selezionare gli appezzamenti.

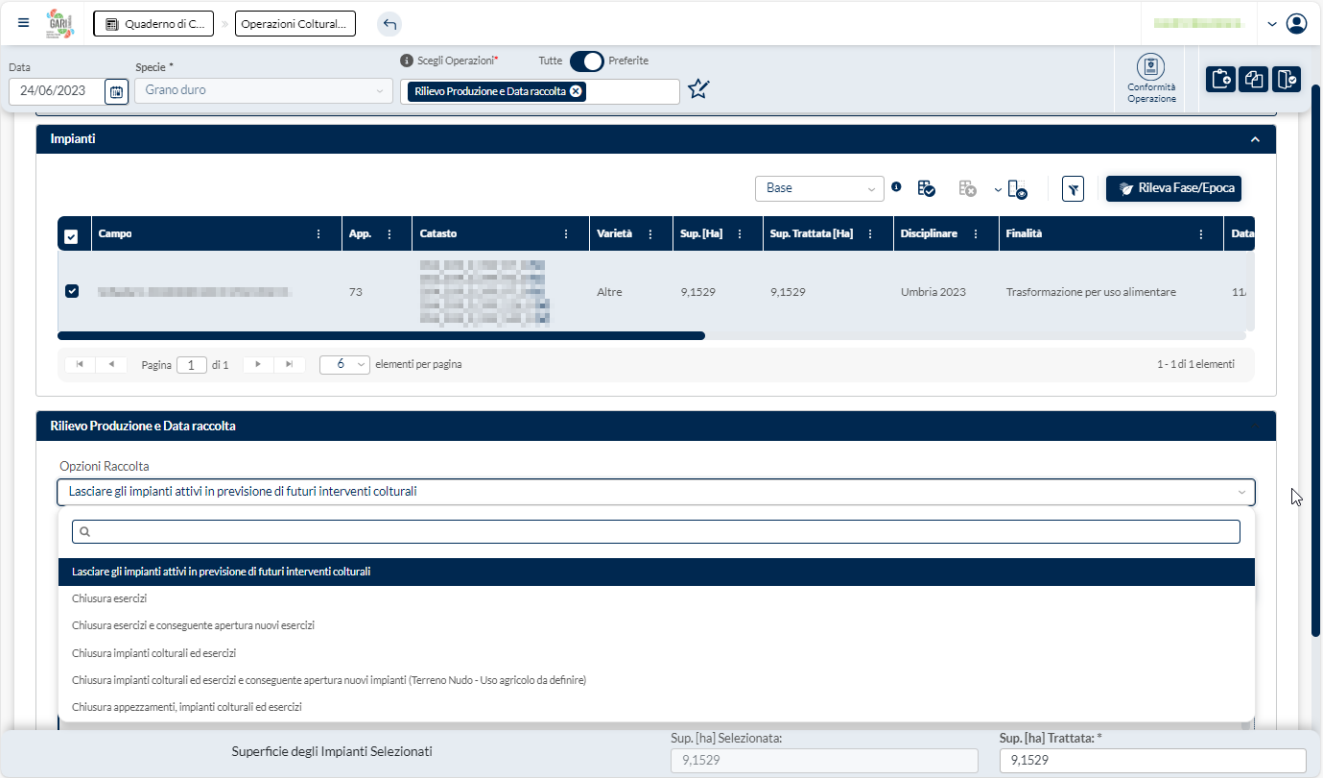

Scegliere tra le **Opzioni Raccolta** proposte:

- **Lasciare gli impianti attivi in previsione di futuri interventi colturali** (es: la gestione di diverse raccolte durante la stessa annata)
- **Chiusura esercizi; Chiusura esercizi con conseguente apertura di nuovi esercizi** (es: raccolta con chiusura esercizio 2023; chiusura 2023 ed apertura esercizio 2024)
- **Chiusura impianti colturali ed esercizi; Chiusura impianti colturali ed esercizi con conseguente apertura di nuovi impianti (Terreno Nudo – Uso agricolo da definire)**, chiude contemporaneamente l'esercizio e l'impianto della coltura raccolta; chiude e genera in automatico un terreno nudo sul quale registrate nuove operazioni (es: anticipazioni colturali oppure con la semina/trapianto di un nuovo impianto per la gestione di un secondo raccolto).
- **Chiusura appezzamenti, impianti colturali ed esercizi**

Per la raccolta sono previste modalità diverse di gestione del dettaglio della raccolta:

- **Raccolta ai fini del Quaderno di Campagna**: E' sufficiente inserire la data di inizio raccolta e selezionare gli appezzamenti, senza indicazione del prodotto raccolto.
- **Raccolta ai fini di una certificazione del prodotto** (es: biologico): Dagli enti certificatori è richiesto anche l'articolo **Prodotto raccolto**, **Quantità raccolta**, **Lotto di produzione** ed eventualmente il **Magazzino di destinazione** e **la data di ingresso** in magazzino.

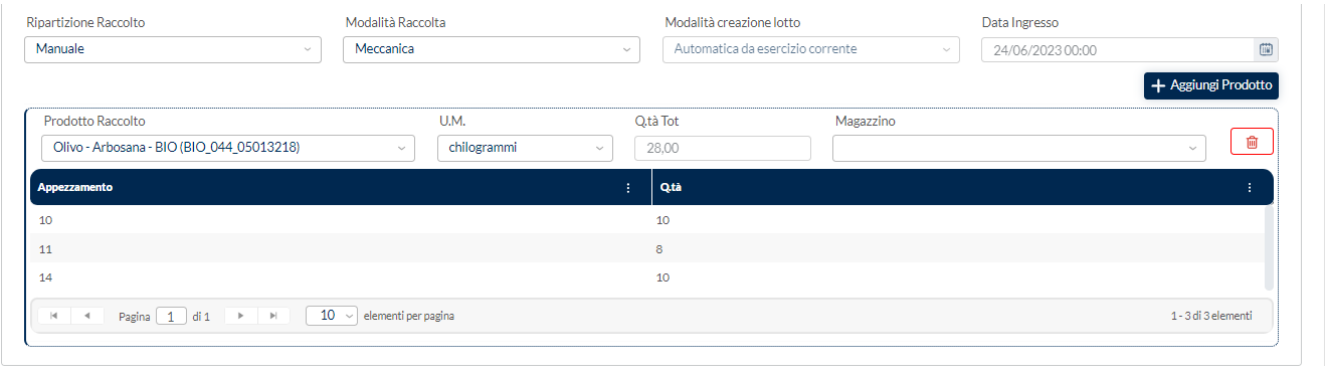

9.7 Lavorazioni e Altre lavorazioni

La registrazione delle lavorazioni (aratura, erpicatura, potatura, etc.) non comportano uno scarico di magazzino, è quindi sufficiente inserire la **data**, la **specie**, **selezionare gli appezzamenti** coinvolti e salvare l'operazione.

Per la specifica lavorazione non presente, utilizzare **Altre Lavorazioni.**

L'attività svolta deve essere indicata nel campo **Descrizione** e nel campo **Note.**

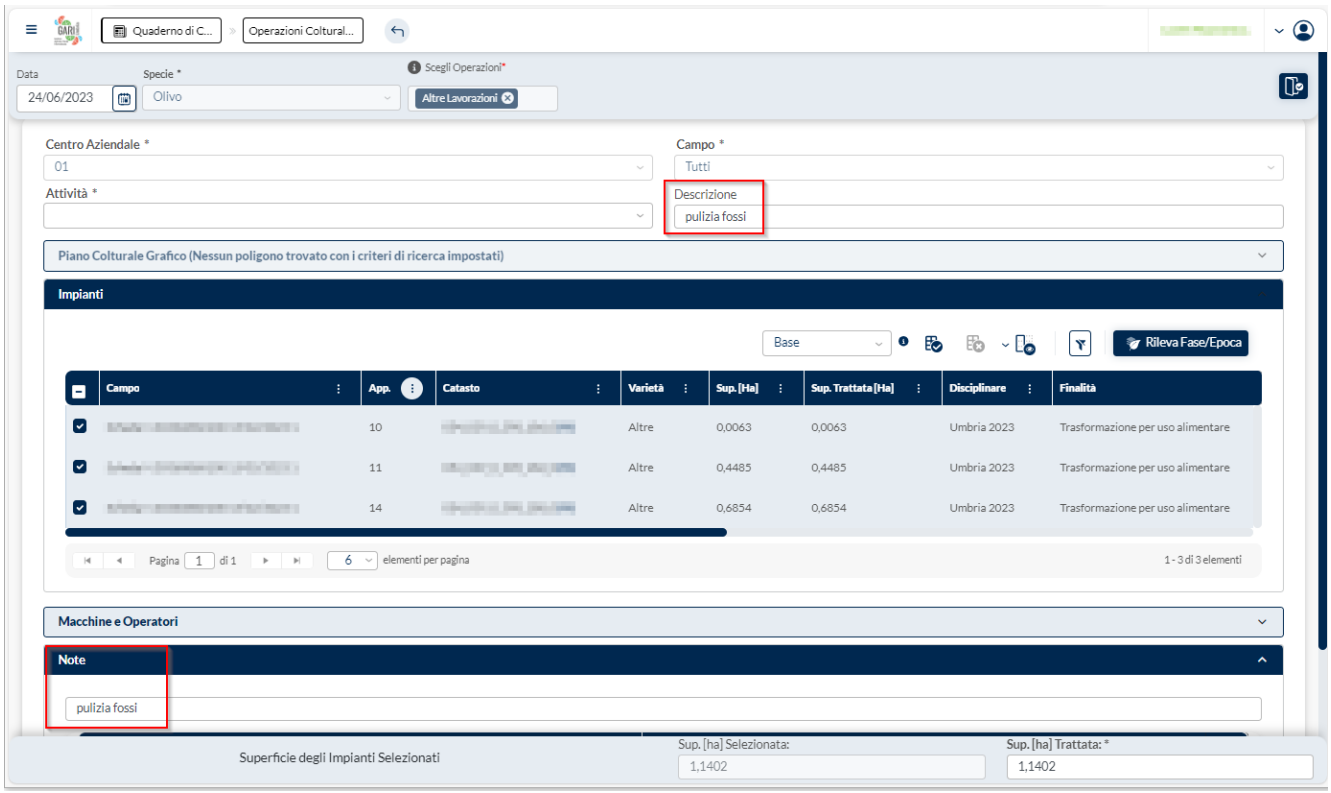

9.8 Verifica conformità

Modulo **Quaderno di Campagna**, Funzione **Verifica Conformità.**

oppure dalla Funzione **Operazioni Colturali**, attraverso il comando **Verifica Conformità**.

La funzione permette di controllare le operazioni già registrate in termini di conformità da etichetta e Disciplinare/Regolamento selezionato.

Compilare i FILTRI ANALISI (Specie vegetale, data Inizio/Fine da verificare, il disciplinare/Regolamento o lasciare come **Indicato nell'operazione**) quindi avviare analisi conformità.

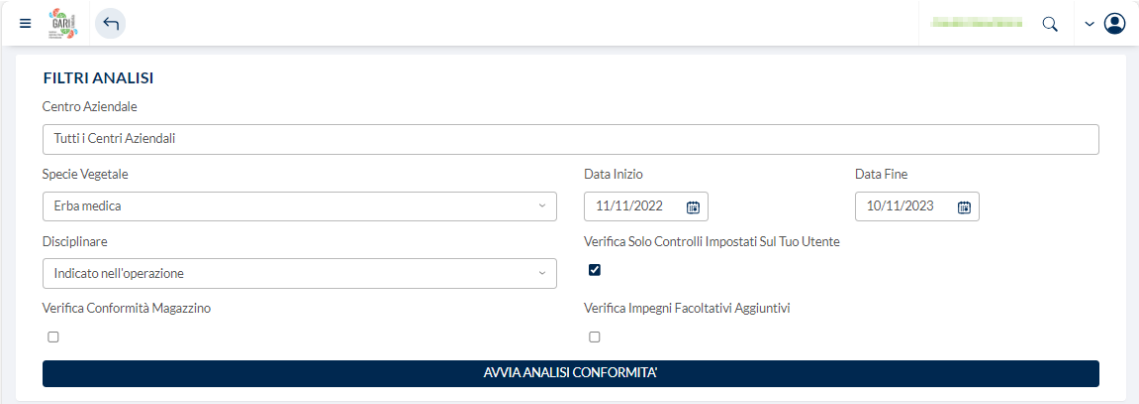

Attendere il caricamento dei risultati che possono essere stampati attraverso comando STAMPA RISULTATO.

Il trattamento non conforme è evidenziato in rosso.

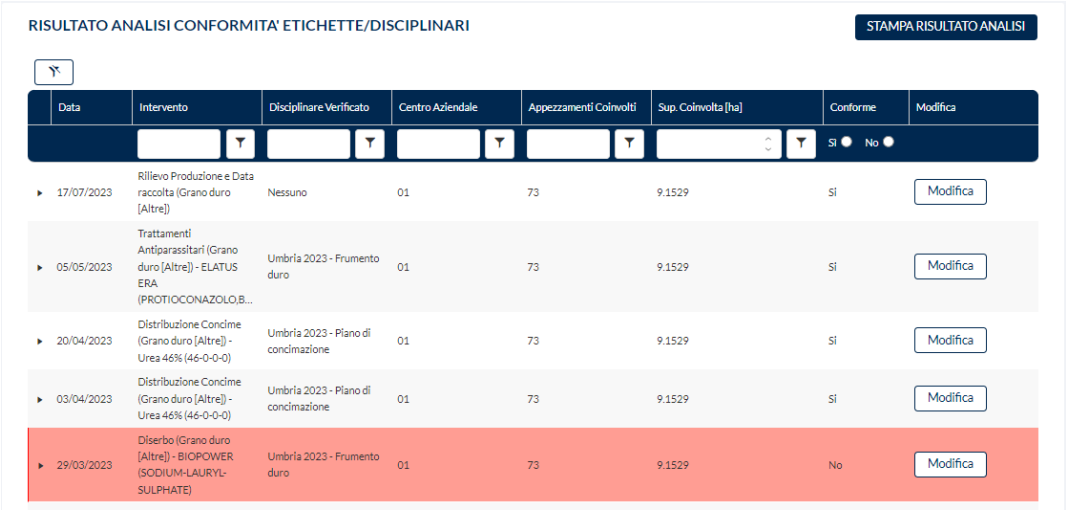

Data	Intervento	Disciplinare Verificato	Centro Aziendale	Appezzamenti Coinvolti	Sup. Coinvolta [ha]	Conforme	Modifica
17/07/2023	Rilievo Produzione e Data raccolta (Grano duro [Altre])	Nessuno	01	73	9.1529	Si	Modifica
05/05/2023	Trattamenti Antiparassitari (Grano duro [Altre]) - ELATUS ERA (PROTIOCONAZOLO,B...	Umbria 2023 - Frumento duro	01	73	9.1529	Si	Modifica
20/04/2023	Distribuzione Concime (Grano duro [Altre]) - Urea 46% (46-0-0-0)	Umbria 2023 - Piano di concimazione	01	73	9.1529	Si	Modifica
03/04/2023	Distribuzione Concime (Grano duro [Altre]) - Urea 46% (46-0-0-0)	Umbria 2023 - Piano di concimazione	01	73	9.1529	Si	Modifica
29/03/2023	Diserbo (Grano duro [Altre]) - BIOPOWER (SODIUM-LAURYL-SULPHATE)	Umbria 2023 - Frumento duro	01	73	9.1529	No	Modifica

Il triangolo nero a sinistra della data per aprire la scheda che riporta il **controllo effettuato** (da etichetta e da DPI/Regolamento) ed il **dettaglio di non conformità.**

Il tasto MODIFICA a destra apre direttamente la pagina dell'operazione colturale per lettura o modifica del dato.

Controllo Effettuato	Conforme	Dettagli NON Conformità
(ETI) Utilizzabilità Prodotto alla data (Revoca/Sospensione/Fine Comm./Fine Scorte)	Si	
(ETI) Registrazione Prodotto su Coltura	Si	
(ETI) Rispettata Epoca/Fioritura/Fase fenologica	Si	
(ETI) Rispetto Carenza alla Data Raccolta	Si	
(ETI) Rispetto Buffer Zone (Fasce Rispetto)	Si	
(ETI) Giustificazione Prodotto su Avversita/Infestante	Si	
(ETI) Dose Massima Prodotto	Si	
(ETI) Dose Minima Prodotto	No	BIOPOWER:La quantità impiegata di BIOPOWER è insufficiente e non conforme all'etichetta del prodotto. La quantità distribuita è di Litri 0,200 mentre quella distribuibile per l'intervento risulta essere non inferiore a Litri 9,153.

10. STAMPA

Al menu stampe si accede dal Modulo **Quaderno di Campagna** Funzione **Operazioni Colturali** attraverso il comando **STAMPA.**

Il menu **STAMPA** è personalizzabile e contiene i formati per la stampa del Quaderno di campagna riconosciuti dagli enti di certificazione (es: SQNPI, biologico, Global Gap,etc.) e dalle Regioni.

Tutti i report possono essere scaricati in PDF e stampati.

10.1 Scheda Biologico

Da menu stampe:

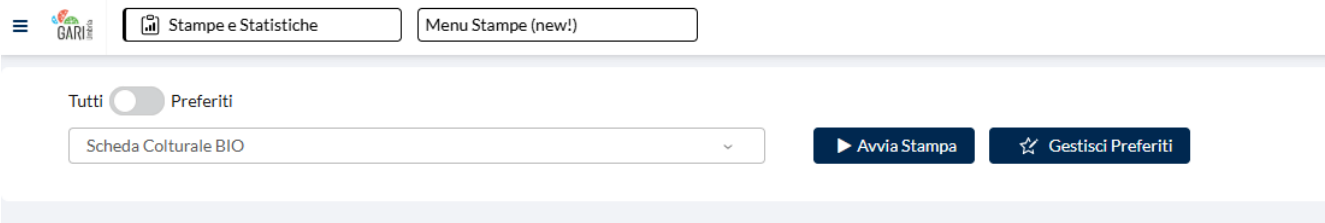

Scegliere la stampa **Scheda colturale BIO** ed impostare i criteri di ricerca per **Coltura (Appezzamenti e Impianti)** e cliccare su **RICERCA.**

Ricordarsi anche dell'intervallo temporale (periodo di validita) in cui il vostro impinato è attivo.

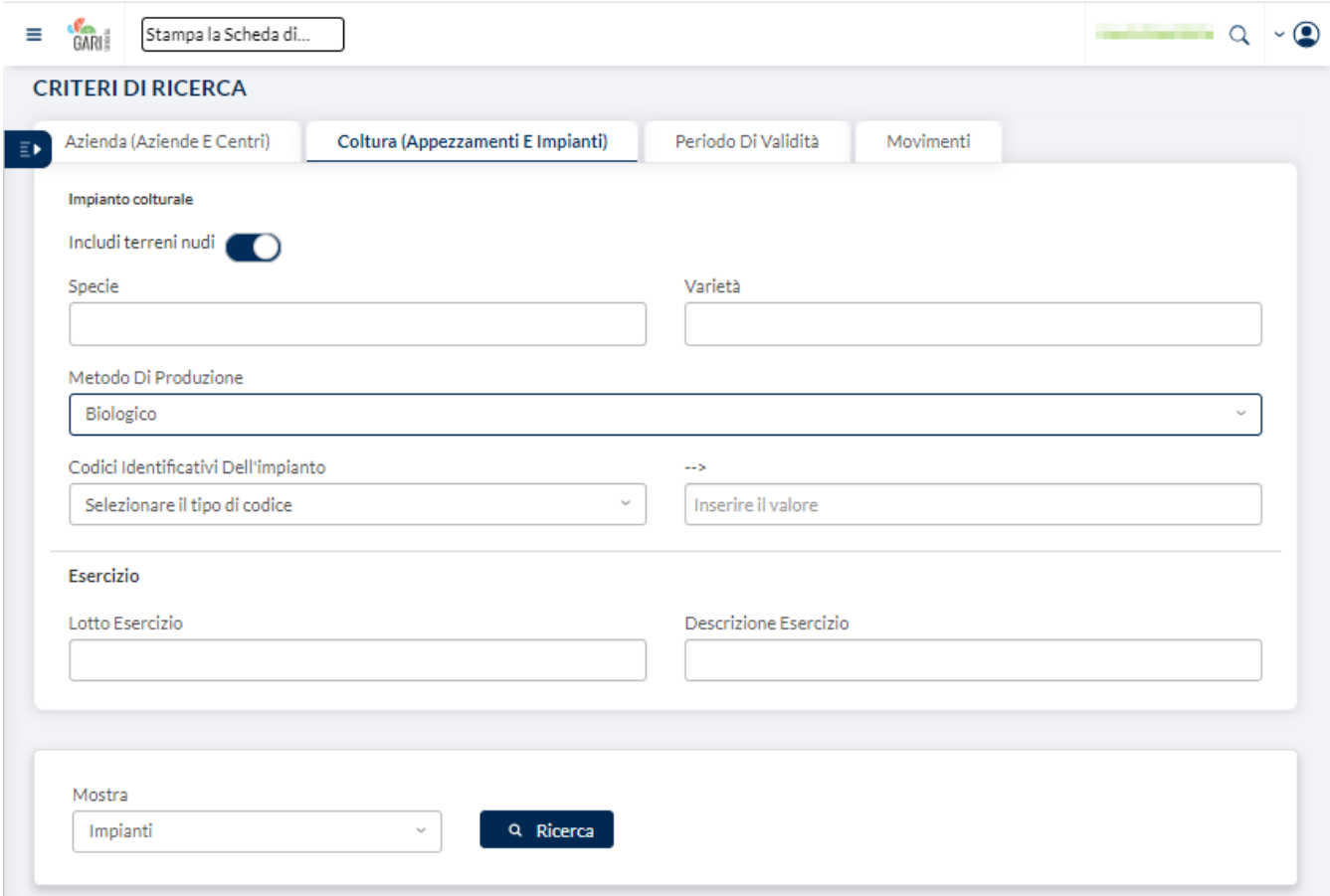

Selezionare gli impianti tra i risultati presentati in ESITO RICERCA e cliccare su Stampa in alto a destra.

Nella pagina di **Riepilogo** impostare **l'opzione di arrotondamento**, **le sezioni che si desiderano stampare** (se non è stato inserito il dato in menù agenda la sezione non verrà stampata), l'intervallo temporale (riquadro rosso) e cliccare sull'icona stampa.

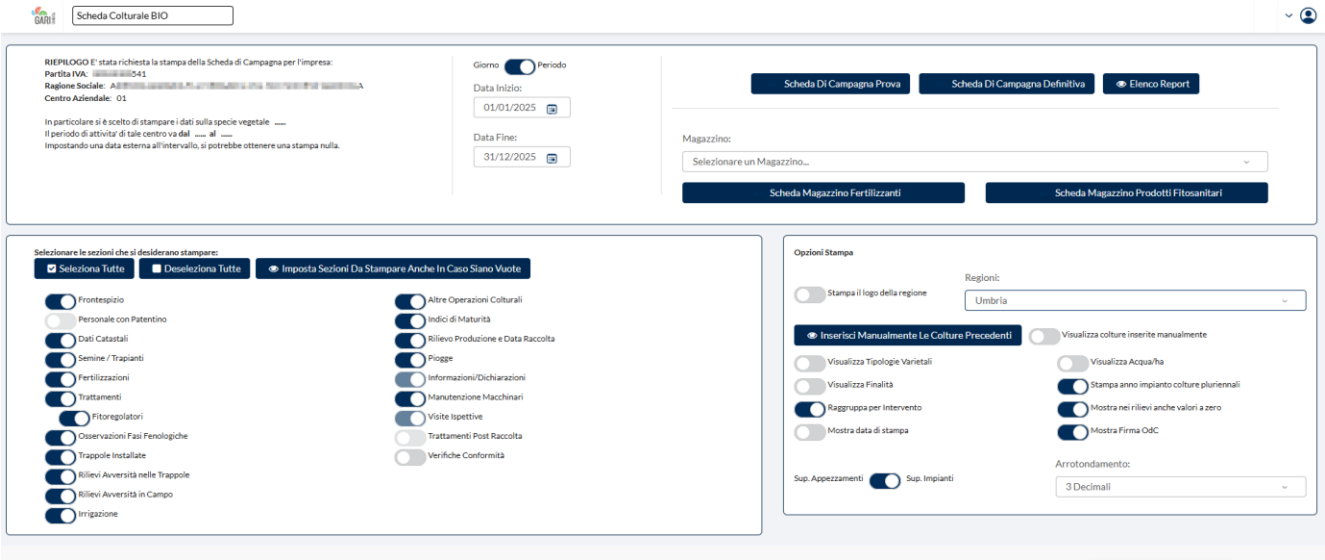

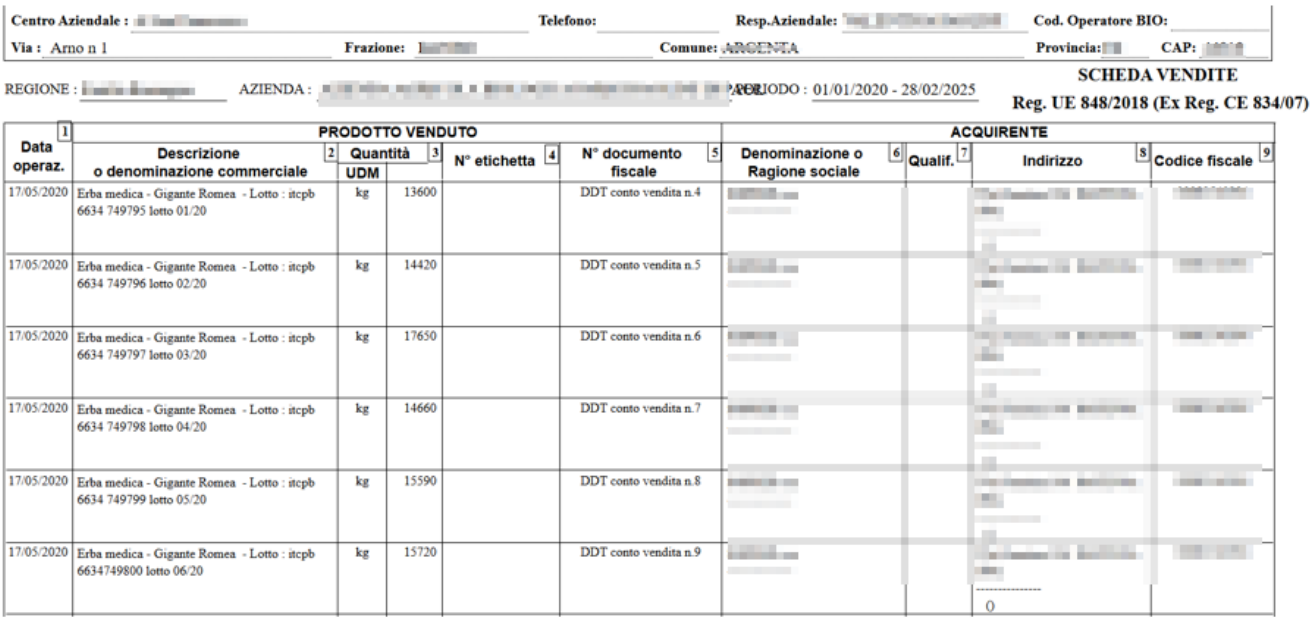

Centro Aziendale : Telefono: Resp.Aziendale: Cod. Operatore BIO:
Via : Arno n 1 Frazione: Comune: ARGENTA Provincia: CAP:

REGIONE : AZIENDA : PERIODO : 01/01/2020 - 28/02/2025

SCHEDA VENDITE
Reg. UE 848/2018 (Ex Reg. CE 834/07)

1 Data operaz.	PRODOTTO VENDUTO 2 Descrizione o denominazione commerciale	3 Quantità UDM		4 N° etichetta	5 N° documento fiscale	ACQUIRENTE 6 Denominazione o Ragione sociale	7 Qualif.	8 Indirizzo	9 Codice fiscale
17/05/2020	Erba medica - Gigante Romea - Lotto : itcpb 6634 749795 lotto 01/20	kg	13600		DDT conto vendita n.4				
17/05/2020	Erba medica - Gigante Romea - Lotto : itcpb 6634 749796 lotto 02/20	kg	14420		DDT conto vendita n.5				
17/05/2020	Erba medica - Gigante Romea - Lotto : itcpb 6634 749797 lotto 03/20	kg	17650		DDT conto vendita n.6				
17/05/2020	Erba medica - Gigante Romea - Lotto : itcpb 6634 749798 lotto 04/20	kg	14660		DDT conto vendita n.7				
17/05/2020	Erba medica - Gigante Romea - Lotto : itcpb 6634 749799 lotto 05/20	kg	15590		DDT conto vendita n.8				
17/05/2020	Erba medica - Gigante Romea - Lotto : itcpb 6634749800 lotto 06/20	kg	15720		DDT conto vendita n.9				
								0	

10.2 Schede materie prime

Menu stampe>scheda materie prime bio

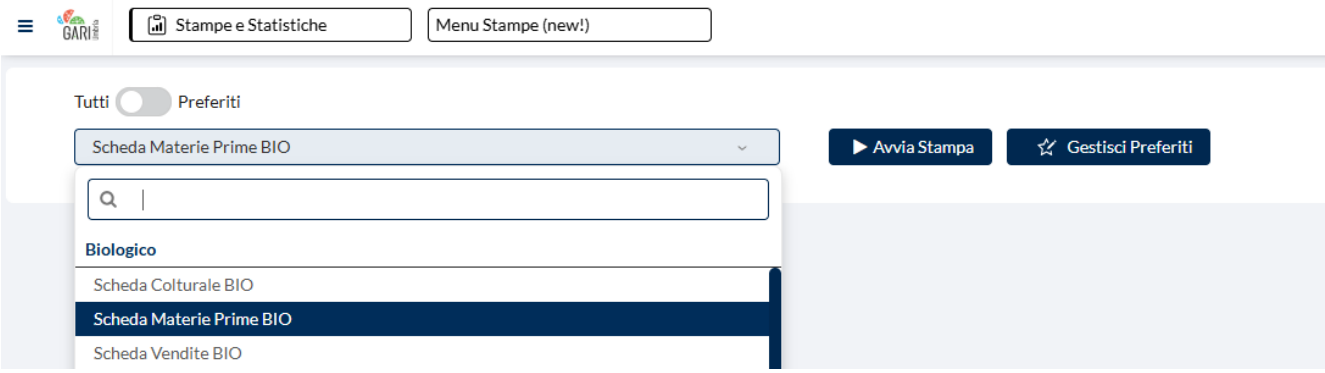

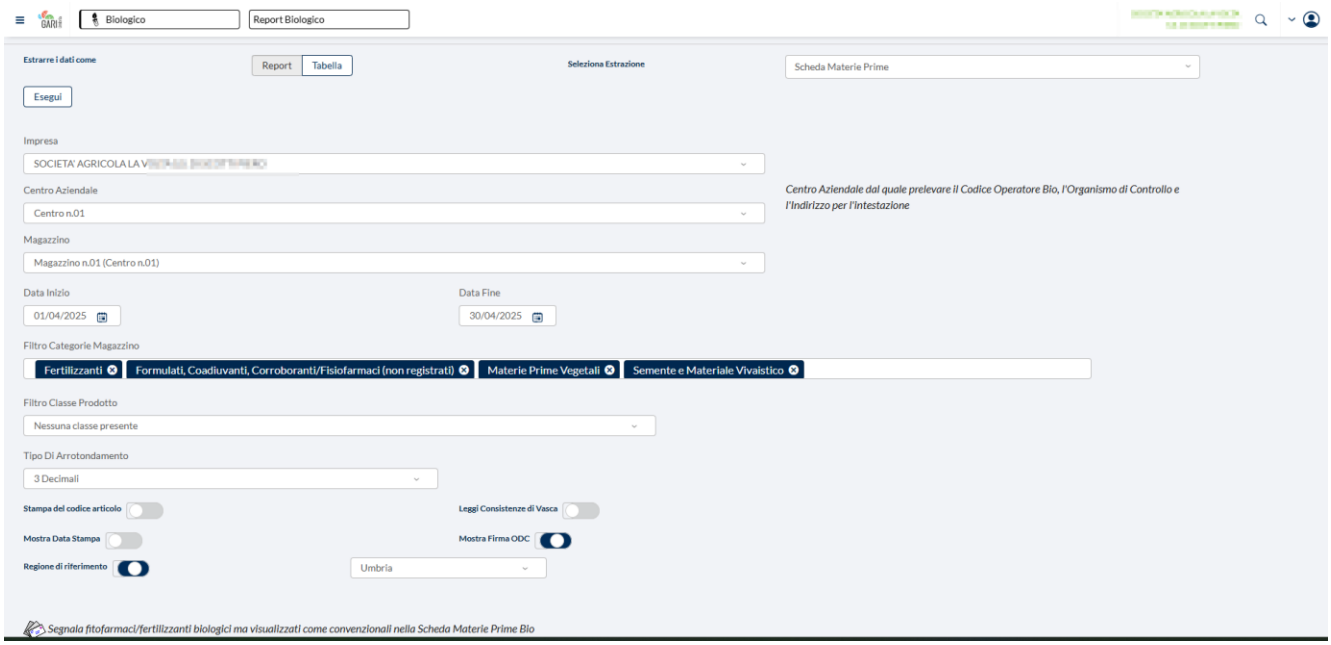

Procedere poi come descritto precedentemente: impostare opzioni di arrotondamento, sezioni da stampare, intervallo temporale.

Si ricorda che verranno riportate in stampe solo le materie prime precedentemente filtrate e che rientrino nel reg biologico 848/2018

Azienda : SOCIETA' A[redacted] **P.IVA:** 03102640541 **CUAA:** 03102640541 **Organismo di Controllo:**

Centro Aziendale : Centro n.01 **Telefono:** **Resp.Aziendale:** EDOARDO [redacted] **Cod. Operatore BIO:** 0

Impegni Aggiuntivi : ACA 12

Via : LOCALITA' LA MOLTA SNC **Frazione:** **Comune:** MASSA MARTANA **Provincia:** PG **CAP:** 06056

REGIONE : Umbria ANNO : 01/04/2025 - 30/04/2025

SCHEDA MATERIE PRIME
Reg. UE 848/2018 (Ex Reg. CE 834/07)

1	PRODOTTO ACQUISITO						FORNITORI			
Data operaz.	Descrizione o denominazione commerciale 2	Quantità 3			N° etichetta 4	N° documento fiscale 5	Denominazione o Ragione sociale 6	Qualif. 7	Indirizzo 8	Codice fiscale 9
		UDM	A.B.	Conv.						
01/04/2025	BORDOLIT 20 PB (ex POLTIGLIA MANICA 20 PB) (Num.Reg.10891)	kg	-0,150							

FIRMA ODC

Umbria Digitale S.c. a r.l.

11. PROFITOSAN

La scheda del singolo prodotto si apre con il tasto

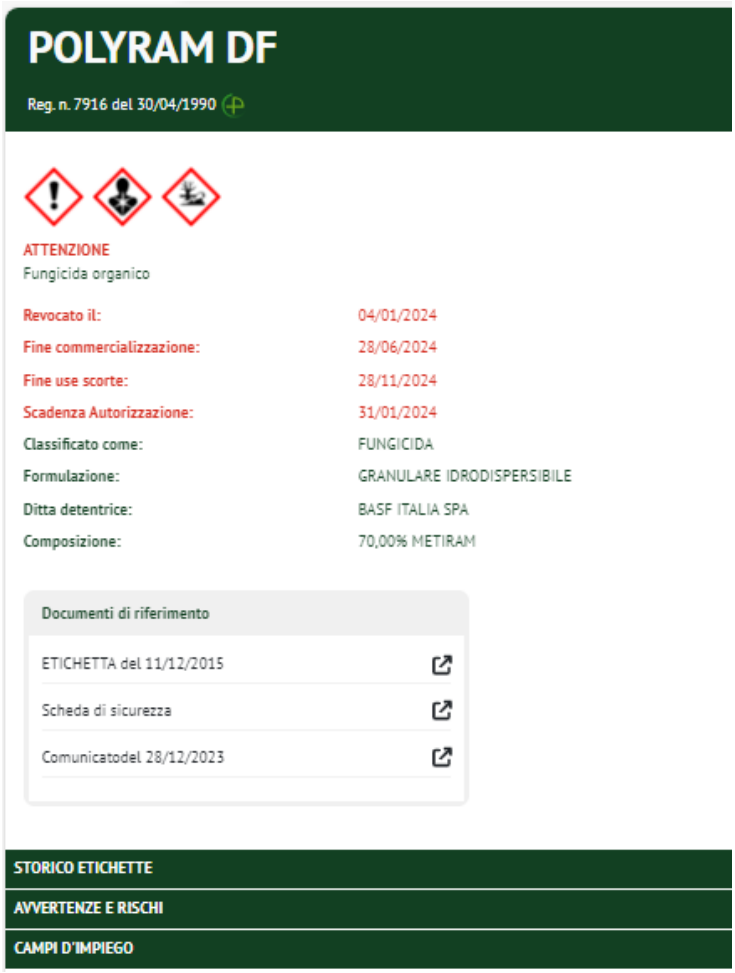

Sono consultabili tutte le informazioni del prodotto:

pittogrammi, scadenza autorizzazione, indicazioni di revoca e data fine utilizzo scorte, classificazione, formulazione, ditta, composizione, etc.

I documenti sono tutti consultabili e scaricabili come pdf, in evidenza:

l'etichetta attualmente in vigore,

la **scheda di sicurezza**,

Decreti Ministeriali e Comunicazioni (es: estensioni di utilizzo, limitazioni temporanee, etc.).

Nella sezione **Storico Etichette** i dati storicizzati delle precedenti etichette.

Campi d'impiego sono le colture su cui è registrato il prodotto.

Click sulla specie per mostrare l'elenco delle avversità, i dosaggi e le limitazioni/indicazioni di utilizzo.